CHAPTER 5

PENUGOLU - A VILLAGE ON THE HILLS

R3A3Z4

In the previous two chapters, we studied about village life in the Krishna delta and on the Telangana plateau region. In this chapter, we will study village life in a very different region – the hills. You may have visited some hills or you may be living on them. Can you describe a hill? What do you find there? What kind of things do people do there?

Fig. 5.1: Hills around Penugolu Village

5.1 Eastern Ghats

Telangana Plateau is a part of the Deccan Plateau, that is marked by the Eastern Ghats on one corner. Eastern Ghats are located on the eastern boarder of Jayashankar district. The hill ranges in Telangana are part of the Western Ghats. Identify the above regions in the district map of Telangana. These hills further spread to states like Chhattisgarh, Andhra Pradesh and Odisha.

Most people living in the hills belong to different tribal communities. These are: Savara, Konda Dora, Gadaba, Gond, Manne Dora, Mukha Dora and Koya. These indigenous people have their own unique cultural heritage. Many of these communities continue to depend on collection of the forest produce & hunting for their livelihood. Their knowledge about the region, the forest and its produce is really vast and deep. However, these

SCERT TELANGANA

అధ్యాయం 5

పెనుగోలు - కొండలపై ఒక గ్రామం

W9S2I3

గత రెండు అధ్యాయాలలో కృష్ణా డెల్టా ప్రాంతంలోని, తెలంగాణా పీఠభూమి ప్రాంతంలోని గ్రామల గురించి తెలుసుకున్నాం. ఈ అధ్యాయంలో మరో భిన్నమైన ప్రాంతం - కొండలలోని గ్రామం గురించి తెలుసుకుందాం. మీరు కొండలపైకి వెళ్ళి ఉండవచ్చు, లేదా అక్కడ నివసిస్తూ ఉండవచ్చు. కొండని చూడండి. అక్కడ ఏం కనపడతాయి? అక్కడి ప్రజలు ఏం చేస్తారు?

చిత్రం 5.1: పెనుగోలు గ్రామం చుట్టు ఉన్న కొండలు

5.1 తూర్పు కనుమలు

దెక్కన్ పీఠభూమిలో తెలంగాణ పీఠభూమి ఒక భాగం. ఈ పీఠభూమికి ఒక మూలన తూర్పు కనుమలు ఉన్నాయి. తెలంగాణలోని కొండలు పశ్చిమ కనుమలలోనివి. అయితే తూర్పు కనుమలు జయశంకర్ జిల్లాకు తూర్పు సరిహద్దున ఉన్నాయి. తెలంగాణ జిల్లాల పటాన్ని చూసి పై ప్రాంతాన్ని గుర్తించండి. ఈ కొండలు ఛత్తీస్‌గడ్, ఆంధ్రప్రదేశ్, ఒడిశా రాష్ట్రాలలోకి విస్తరించి ఉన్నాయి.

కొండలలో ఉండే అధికశాతం ప్రజలు వివిధ గిరిజన తెగలకు చెందిన వాళ్ళు సవర, కొండ దొర, గదబ, గోండు, మన్నె దొర, ముఖ దొర, కోయ. ఈ స్థానిక ప్రజలకు తమదైన ప్రత్యేక సాంస్కృతిక వారసత్వం ఉంది. చాలా మంది అటవీ ఉత్పత్తుల సేకరణ మీద, వేట మీద ఆధారపడి జీవిస్తున్నారు. ఈ ప్రాంతం వారికి అడవి, అటవీ సంపద గురించిన జ్ఞానం చాలా అపారమైనది, లోతైనది. అయితే ఈ

SCERT TELANGANA

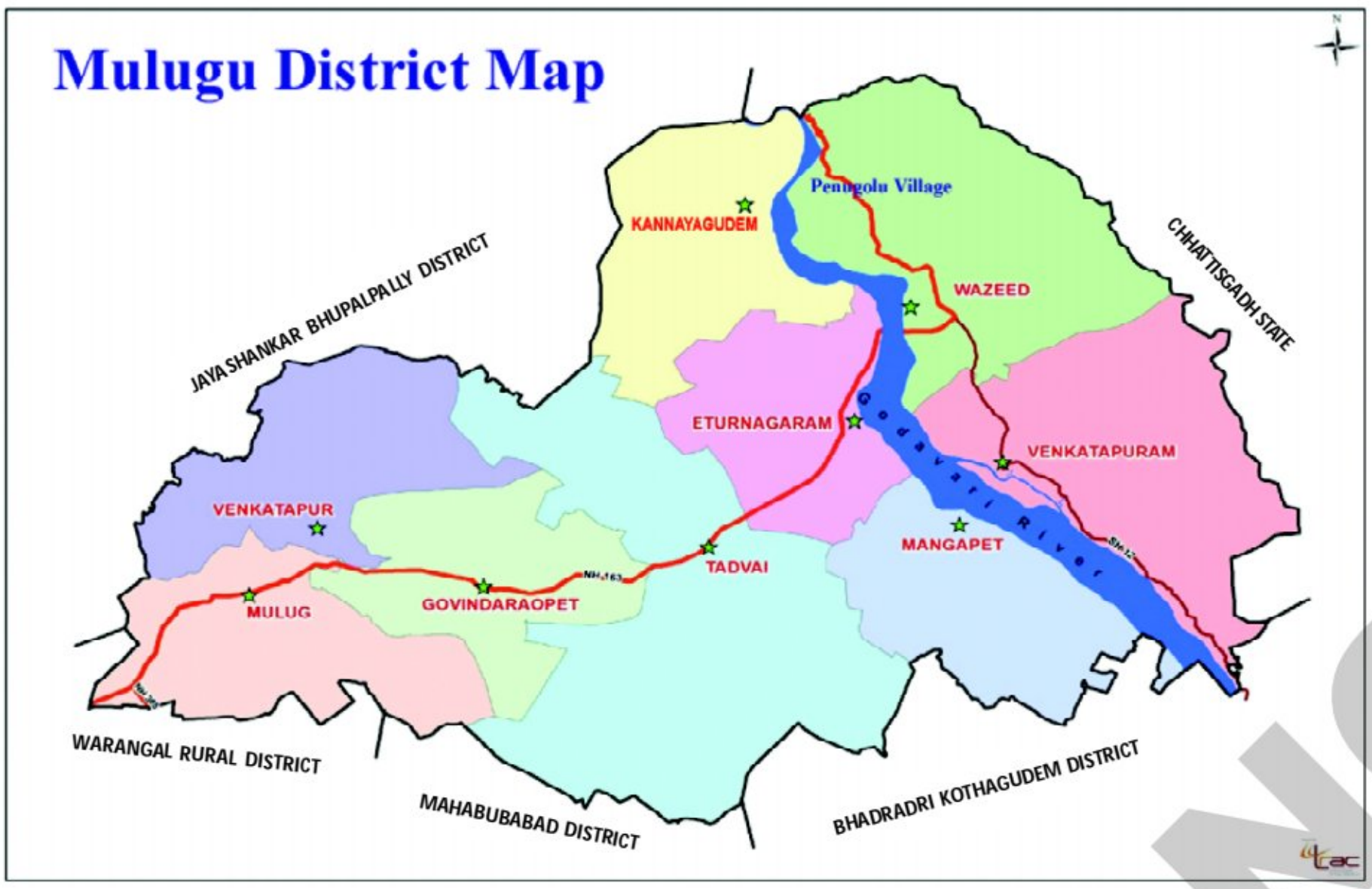

Map 1: Location of Penugolu Village in Mulugu District

communities face many disruptions today that are threatening their way of life. We would discuss some of these issues in this chapter.

Penugolu village in Wazeed mandal lies on hills that are on the banks of River Godavari. (See map 1) The community that live here are Koyas. Koya means "a good person living on the hills". They speak Koya language and this community is spread out on the hills upto the adjoining states surrounding them such as Odisha, Chhattisgarh and Andhra Pradesh. At the same time, many Koyas have migrated away from the hills and now live in Adilabad, Karimnagar, Warangal and some parts of East Godavari. They do not anymore speak Koya language but have adopted Telugu.

This village is surrounded by hills (guttalu) that have names like Karre gutta or Nallagutta - Chattisgarh in the North, Vankamamidi gutta in the south, Kallu Kuntala gutta in the east and Chinna Kummari Lanka, Pedda Kummari Lanka in the west. Locate these hills on the map above.

Wazeed is situated on the confluence of the stream Nallandevi Vagu (from Nallagutta) that flows down from the north and joins the Godavari. From Wazeed, we reached Gummadi Doddi village which is located at the foot of the hills. A path from this village led us up the hills. The path was very steep, narrow and slippery. We also saw the famous Bogatha water fall near Cheekupalli on the way. As we climbed the hills, we saw thick forests and occasional big patches of cleared land. These clearances are the fields that lie scattered across the hills. These fields with red soil were on the slopes and not very fertile. There were plenty of stones and pebbles. It is located 11 kilometers away from mandal head quarter at Wazeedu.

Fig. 5.2: Bogatha Water falls

SCERT, TELANGANA

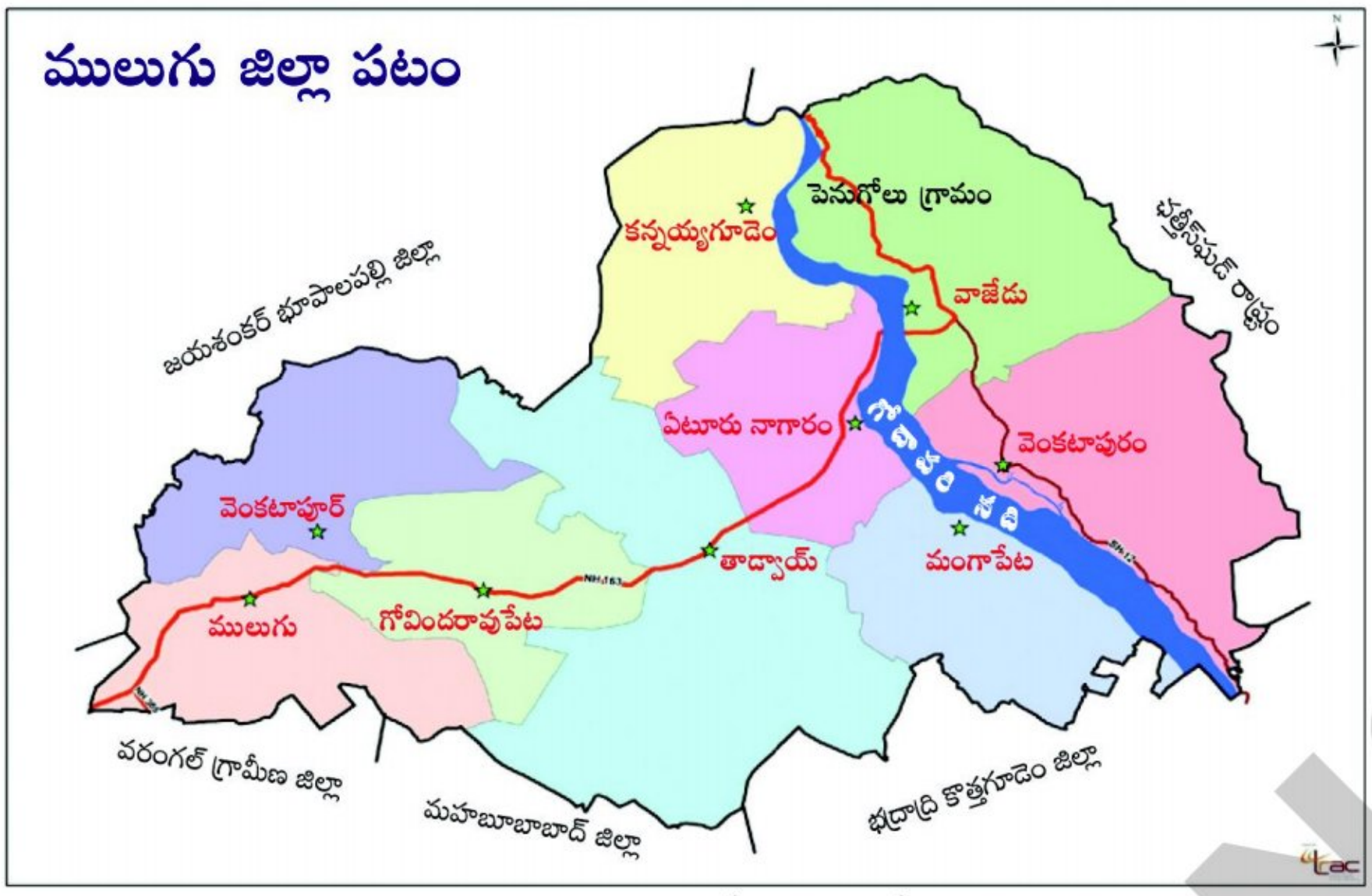

పటం 1: ములుగు జిల్లాలోని పెనుగోలు గ్రామం

తెగలు ప్రస్తుతం వాళ్ళ జీవితాలను ఛిద్రం చేసే అనేక సమస్యలను ఎదుర్కొంటున్నారు. వీటిల్లో కొన్నింటిని ఈ అధ్యయంలో తెలుసుకుందాం.

వాజేడు మండలంలో గోదావరి నది తీరంలోని కొండలలో పెనుగోలు ఉంది. (పటం 1 చూడండి). ఇక్కడ కోయతెగ వాళ్ళు నివసిస్తున్నారు. కోయ అంటే "కొండలలో ఉంటున్న మంచి మనిషి' అని అర్థం. వీళ్ళు కోయ భాష మాట్లాడతారు. వీళ్ళు పక్క రాష్ట్రాలైన ఒడిశా, ఛత్తీస్‌గఢ్, ఆంధ్రప్రదేశ్ కొండలలో ఉన్నారు. అయితే, చాలా మంది కోయలు కొండల నుంచి వలస వెళ్ళిపోయి ఆదిలాబాదు, కరీంనగర్, వరంగల్, తూర్పు గోదావరిలోని కొన్ని ప్రాంతాలలో స్థిరపడ్డారు. ఇటువంటి వాళ్ళు ఇప్పుడు కోయ భాష మాట్లాడరు. తెలుగునే తమ భాషగా చేసుకున్నారు.

ఈ గ్రామానికి చుట్టూ గుట్టలు ఉన్నాయి. ఉత్తరాన ఛత్తీస్‌గఢ్‌లో కర్రెగుట్ట లేదా నల్లగుట్ట, దక్షిణాన వంక మామిడి గుట్ట, తూర్పున కల్లు కుంటల గుట్ట, పడమరన చిన్న కుమ్మరి లంక, పెద్దకుమ్మరి లంక ఉన్నాయి. పై పటంలో ఈ గుట్టలను చూపించండి.

వాజేడు మండలం ఉత్తరాన నల్లగుట్ట నుంచి ప్రవహించే నల్లందేవి వాగు, గోదావరి నదిని కలిసే ప్రాంతంలో ఉంది. వాజేడు కొండల నుంచి దిగువున ఉన్న గుమ్మడి దొడ్డె గ్రామం చేరుకున్నాం. ఇక్కడి నుంచి ఒక కాలిబాట కొండలపైకి వెళుతుంది. ఈ బాట చాలా ఏటవాలుగా, సన్నగా, జారుతూ ఉంది. ఎవరైన పొరపాటున కాలు జారితే కింద లోయలో పడతారు. దారిలో చీకుపల్లి దగ్గర ప్రఖ్యాత బొగతా జలపాతం చూశాం. పైకి ఎక్కుతున్న క్రమంలో దట్టమైన అడవులు, చెట్లు నరికి శుభ్రం చేసిన భూములు కనిపించాయి. ఇలా ఖాళీ చేసిన భూములు కొండలలో అక్కడక్కడ ఉన్నాయి. ఎర్రనేలతో వాలుగా ఉన్న ఈ భూములు అంత సారవంతమైనవి కావు. ఆ పొలం నిండా పెద్ద, చిన్న రాళ్ళు చాలా ఉన్నాయి. మండల కేంద్రమైన వాజేడుకి ఇది 11 కిలోమీటర్ల దూరంలో ఉంది.

చిత్రం 5.2: బొగతా జలపాతం

SCERT, TELANGANA

Fig 5.3: A field near the forest

In the hills, it stops raining around November. The Koyas then use their axes to clear patches of forest in the month of December. They allow the logs of wood to lie there and dry on the field for a few months. These are then burnt in April or May just before it rains. When the rainy season starts, the ground is covered with ashes. With the arrival of rain in June, people dibble seeds with the help of digging sticks. This way, they sow seeds of many crops together by broadcast method – spreading the seeds on the ground. They do not use plough or hoe nor do they use any fertiliser.

One of the reasons for not using plough on the hill slopes is that this would loosen the soil too much. This would lead to easy run off of the top soil during the rains. This would make the fields infertile. It is the top soil that is most fertile of the field. Farmers want the ashes and dead leaves to

5.2 Podu

Koyas grow crops using a distinct technique called 'Podu'. Podu is a traditional practice of farming in hilly regions. This is called "shifting agriculture" or "Jhum cultivation". It is also practiced by tribes like Konda Reddy. This practice of shifiting cultivation is also done in states like Andhra Pradesh, Chhattisgarh, Arunachal Pradesh etc.

Each village has a specified area or hill that they can use for farming. Within this area, people clear a patch of forest and burn it. Then, they grow crops on these fields for a few years. After that, they leave that patch of land and allow the forest to grow again. Meanwhile, they move to another site in that area where they clear another patch of forest land to grow crops for a few years. This way, their farms keep shifting every few years and they return to these plots after many years.

Fig. 5.4: Dibbling seeds with a digging stick, a photograph from 1940

SCERT, TELANGANA

 Government's Gift for Students' Progress

చిత్రం 5.3: అడవి దగ్గర ఉన్న ఒక చేను

5.2 పోడు

కోయలు పోడు అనే ప్రత్యేక పద్ధతిలో పంటలు సాగు చేస్తారు. కొండలలో వ్యవసాయం చేసే ప్రత్యేకమైన విధానం ఇది. దీనినే “ఝూమ్”సాగు అని కూడా అంటారు. కొండ రెడ్డి వంటి ఇతర తెగలు కూడా ఈ పద్ధతిని ఆచరిస్తాయి. ఈ పద్ధతి ఆంధ్రప్రదేశ్, చత్తీస్‌గఢ్, అరుణాచల్ ప్రదేశ్ వంటి రాష్ట్రాలలో కూడా ఉంది.

ప్రతి గ్రామానికి వాళ్ళు వ్యవసాయానికి ఉపయోగించుకోటానికి నిర్ధిష్ట కొండలు, ప్రాంతం ఉంటాయి. ఈ ప్రాంతం లోపల వాళ్ళు కొంత అడవిని నరికి తగలబెడతారు. కొన్ని సంవత్సరాలపాటు ఈ భూమిలో వ్యవసాయం చేస్తారు. ఆ తరువాత దానిని వదిలిపెట్టి మళ్ళీ అడవి పెరగనిస్తారు. ఈ లోగా వాళ్ళు అడవిలోని ఇంకో ప్రాంతంలో చెట్లు నరికి అక్కడ వ్యవసాయం చేస్తారు. ఈ విధంగా వాళ్ళ సాగుభూమి ప్రతి కొన్ని సంవత్సరాలకు మారుతూ ఉంటుంది, ఒకసారి సాగు చేసిన భూమికి చాలా సంవత్సరాల తరువాత మళ్ళీ తిరిగి వస్తారు.

కొండలలో నవంబర్‌లో వానలు ఆగిపోతాయి. కోయలు డిసెంబరు నెలలో గొడ్డళ్ళతో కొంత ప్రాంతంలో చెట్లు నరుకుతారు. కొట్టిన చెట్ల కొమ్మలు కొన్ని నెలలపాటు ఎండనిస్తారు. ఈ ఎండిన కొమ్మలను వానలకు ముందు ఏప్రిల్ లేదా మే నెలలో తగలబెడతారు. వానలు పడే సమయానికి నేల బూడిదతో కప్పి ఉంటుంది. జూన్‌లో వానలు పడినప్పుడు కట్టెలతో పొడిచి విత్తులు విత్తుతారు. ఈ విధంగా వాళ్ళు అనేక రకాల పంట విత్తనాలు కలిపి చల్లుతారు. వాళ్ళు నాగలిగాని, పారగాని ఉపయోగించరు. ఎటువంటి రసాయనిక ఎరువులు ఉపయోగించరు.

నేలను దున్నితే మట్టి వదులయి, వానలు పడినప్పుడు పైమట్టి తేలికగా కొట్టుకుపోతుంది. కాబట్టి నేలను దున్నరు. పైమట్టి కొట్టుకుపోతే నేల సారాన్ని కోల్పోతుంది. బూడిద, రాలిన ఆకులతో పై మట్టి సారవంతంగా ఉంటుంది. కాబట్టి అది కొట్టుకు

చిత్రం 5.4: కట్టెతో పొడిచి విత్తులు విత్తటం, 1940ల నాటి ఫోటో

SCERT, TELANGANA

remain on the land and not get washed away. The main crops of the area are Jowar (jonnalu) *maize* (*mokka jonna*), tubers (*dumpalu*), millets (*samalu, korralu, sode*, *adusulu*); seasamum (nuvvulu), pulses like red gram (*kandulu*), green gram (*pesarlu*); vegetables like Brinjal (*vankaya*); chillies *(pachimirapa); gongura* etc. They grow mixed crops without any irrigation. The total produce normally provides them with enough food for about six months.

Since these fields are close to the forests, they easily attract animals and birds of the region. The Koyas build manche to guard their fields until December.

We read earlier that farming is done on a particular plot of land for a few years and in another one for the next few years. In olden days, on an average, each family cleared 2 to 2.5 acres of forest land. The average yield of *jowar* per acre of *podu* field is 250 kilograms. So, each family harvested about 600 kilograms of jowar apart from 150 to 250 kilograms of small millets. Earlier, larger forest areas were available in the hills. But now, the area available for podu has decreased to about 1 - 1.5 acres. This has led to reduced availability of food grains for each family. At the same time, people are forced to come back to the same plot of land earlier than before because the forest area has decreased. The rotation cycle has also become smaller so the soil is not able to recover its fertility as earlier.

- What are the reasons for the reduction of podu area in recent years?
- Do you know of any other method of raising crops on slopes of hills?
- In what way does the ash help in the growing of the crops?
- Do wild animals attack farms in your area too? What do people do to protect the crops?

5.3 Vegetable garden in the back yard

From a distance, we could notice that the houses in this village had neat bamboo fences around the backyard with leveled land. This was quite unlike the stony and sloping agricultural fields. This back-yard provided a space for a small kitchen garden. In this small plot, they planted a few vegetables like beans, gourd, chillies and fences had climbers like pumpkin. At times poultry was also kept within these fences. Some of them rear goats, sheep, cattle and dogs.

Fig. 5.5: Kitchen garden fence and the houses

SCERT, TELANGANA

పోకుండా కాపాడాలని రైతులు ప్రయత్నిస్తారు. వీళ్ళు పండించే ముఖ్యమైన పంటలు : జొన్నలు, మొక్క జొన్నలు, దుంపలు; చిరుధాన్యాలు (సామలు, కొర్రలు, పప్పు (*sode*), అడుసులు)నువ్వులు; కందులు, పెసర్లు వంటి అపరాలు; వంకాయ, పచ్చిమిరప, గోంగూర వంటి కూరగాయలు. ఎటువంటి సాగునీరు లేకుండా మిశ్రమ పంటలు పండిస్తారు. వాళ్ళు పండించే పంటలు సాధారణంగా ఆరు నెలల వరకు ఆహారంగా సరిపోతాయి.

ఈ పొలాలు అడవి పక్కన ఉంటాయి. కాబట్టి అందులోని జంతువులు, పక్షులు పంటల మీద దాడి చేస్తాయి. కోయలు పొలాల్లో మంచెకట్టి డిసెంబరు వరకు పంటను కాపాడుకుంటారు.

ఒక పొలాన్ని కొన్ని సంవత్సరాలు సాగుచేసిన తరువాత కొన్ని సంవత్సరాలు మరొక పొలానికి వెళతారని చదివాం. పాత రోజుల్లో సగటున ప్రతి కుటుంబం 2-2.5 ఎకరాల అటవీ భూమిని సాగు చేసేది. పోడు పద్ధతిలో జొన్న సగటున ఎకరానికి 250 కిలోల దిగుబడిని ఇస్తుంది. అంటే ప్రతి కుటుంబానికి 600 కిలోల జొన్నలతో పాటు 150-250 కిలోల చిరుధాన్యాలు లభించేవి. గతంలో కొండలలో ఎక్కువ విస్తీర్ణం పోడుకు లభించింది. కాని ప్రస్తుతం 1-1.5 ఎకరాలు మాత్రమే ఉంది. దాంతో ప్రతి కుటుంబానికి అందే ఆహారధాన్యాలు తగ్గి-పోయాయి. అటవీ విస్తీర్ణం తగ్గిపోవటం వల్ల పోడు చేసి వదిలిపెట్టిన ఒక ప్రాంతానికి గతంలో కంటే త్వరగా తిరిగి రావలసి వస్తోంది. ఈ సమయం తగ్గిపోవటం వల్ల నేల గతంలో మాదిరి తన సారాన్ని పూర్తిగా తిరిగి పొందలేక పోతోంది.

ఇటీవల కాలంలో పోడు విస్తీర్ణం తగ్గటానికి కారణాలు ఏమిటి?

- కొండవాలుల్లో పంటలు సాగు చెయ్యటానికి ఇతర పద్ధతులు మీకు తెలుసా?
- పంటల ఎదుగుదలకు బూడిద ఏ విధంగా సహాయపడుతుంది?
- మీ ప్రాంతంలో కూడా పంటలపై అడవి జంతువులు దాడి చేస్తాయా? అటువంటప్పుడు పంటల రక్షణకు ప్రజలు ఏం చేస్తారు?

5.3 పెరటిలో కూరగాయల తోట

ఈ గ్రామంలో ఇళ్ళ చుట్టు వెదురు కంచెలు ఉన్నాయని దూరం నుంచే గమనించాం. వ్యవసాయ భూములు వాలుగా, రాళ్ళతో ఉన్నాయి కానీ ఇంటి చుట్టూ ఉన్న స్థలం చదును చేసి ఉంది. ఇంటి చుట్టు ఉన్న ఈ స్థలంలో కూరగాయలు పండిస్తారు. ఈ తక్కువ విస్తీర్ణంలోనే చిక్కుళ్ళు, బీర, సొరవంటి తీగ జాతి కూరలు, మిరప వంటివి సాగు చేస్తారు. కంచెపై గుమ్మడి తీగలు వంటివి ఉన్నాయి. కొంతమంది ఈ పెరట్లో కోళ్ళను కూడా పెంచుతారు. మరి కొంత మంది మేకలు, గొర్రెలు, పశువులు, కుక్కలు వంటివి పెంచుతారు.

చిత్రం 5.5.: ఇల్లు, ఇంటి చుట్టూ కూరగాయల తోట, దడి

SCERT, TELANGANA

Fig. 5.6: Taking cattle to graze

5.4 Non timber Forest products

When we spoke with people at the village we realised that grain and vegetables produced in the podu lands or their back yard is insufficient for the families to survive throughout the year. Hence, collection of forest produce and hunting plays a vital role in their livelihood. The forest is a great storehouse and, over hundreds of years, the people have identified all the various available edible food and sources of medicine. The people in this village depend upon the forest throughout the year. The tribal calendar is marked by various seasons for various edible fruits, tubers, nuts, green leaves and even for hunting small animals. For any illnesses, either for humans or animals, their knowledge of the medicinal plants collected from the forest provides the remedies.

Except for a few months during and after harvest, tribal women and children are engaged in collection of edible forest produce. The two important forest products that they collect are honey and bamboo shoots. They collect honey from trees, climbing them with the help of a single pole ladder. Tender bamboo shoots called '*kari kommulu*' are collected from the tips of the bamboo bushes. The shoots are cooked after the outer layers are removed. This is a great delicacy. Another important source of food for the families is the juice of palm tree, (thati kallu) especially in summers. All the members of a family work together on the fields, in the forest and in hunting. Men do more work related to cattle rearing and agriculture. Women and children attend to gathering food from the forest and basket weaving.

Some of the forest products are also sold in the weekly market - Santha. For example, Mahua seeds are a major item that they sell in the market. With the money they earn by selling these products, they purchase items of daily needs like clothes and other requirements.

- What forest products do you eat? Make a list.
- Have you collected any edible things from the forest? If so share your experiences.

5.5 Drinking water

There are many natural springs that provide drinking water to the people in this village. Then, there are streams that flow through the hills and later join rivers like Sabari or Godavari. It is hard to dig wells on the hills because of the rocks. The water at the springs lasts throughout the year,

SCERT, TELANGANA

చిత్రం 5.6: పశువులను మేపటానికి తీసుకెళ్తున్న రైతులు

5.4 కలపేతర అటవీ ఉత్పత్తులు

గ్రామస్తులతో మాట్లాడినప్పుడు చేలు, పెరటి దొడ్డిలో పండే ఆహార ధాన్యాలు, కూరగాయలు కుటుంబ అవసరాలకు సంవత్సరమంతా సరిపోవని తెలిసింది. కాబట్టి వాళ్ళ జీవనోపాధిలో అటవీ ఉత్పత్తుల సేకరణ, వేట ముఖ్య భాగం అయ్యాయి. అడవులు గొప్ప బాంఢాగారాలు వంటివి. వందల ఏళ్ల సహజీవనంలో అడవిలో దొరికే అనేక రకాల ఆహారాలను, మూలికలను గుర్తించారు. ఈ గ్రామంలోని ప్రజలు సంవత్సరం పొడవునా అడవిపై ఆధారపడి బతుకుతారు. గిరిజనుల కాలమానిని (క్యాలెండరు) రకరకాల పళ్ళు, దుంపలు ఆకులు చిన్న జంతువుల వేటకి సంబంధించిన కాలాలతో నిండి ఉంటుంది. మనుషులకు గానీ, పశువులకు గానీ జబ్బు చేసినప్పుడు అడవిలోని మూలికలకు సంబంధించిన జ్ఞానంతో వాళ్ళు చికిత్స చేసుకుంటారు.

పంటకోతకి కొన్ని నెలలు ముందు, తరువాత తప్పించి గిరిజన మహిళలు, పిల్లలు అడవి నుంచి ఆహార ఉత్పత్తుల సేకరణలో మునిగి ఉంటారు. అడవి నుంచి సేకరించే తేనె, వెదురు చిగుళ్ళు రెండు ముఖ్యమైన ఆహార వనరులు. ఒక్క వెదురుతో చేసిన నిచ్చెనతో చెట్లు ఎక్కి తేనె సేకరిస్తారు. లేత వెదురు చిగుళ్ళను 'కరి కొమ్ములు' అంటారు, వీటిని వెదురు పొదల చివర్ల నుంచి సేకరిస్తారు. పై పొర తీసేసిన తరువాత ఈ చిగుర్లను వండుతారు. ఇది చాలా రుచికరమైన వంట. ఈ కుటుంబాలకు మరొక ముఖ్యమైన ఆహారం ప్రత్యేకించి వేనవిలో తాటికల్లు. కుటుంబ సభ్యులందరూ కలిసి చేలల్లో, అడవిలో, వేటలో కలిసి పని చేస్తారు. వ్యవసాయం, పశుపోషణలో ఎక్కువ పనులు మగవాళ్ళు చేస్తారు. అటవీ ఉత్పత్తుల సేకరణ, బుట్టలు అల్లటం వంటి పనులు ఆడవాళ్ళు, పిల్లలు చేస్తారు.

కొన్ని అటవీ ఉత్పత్తులను వారం వారం జరిగే సంతలలో అమ్ముతారు. ఉదాహరణకు ఈ సంతలలో ప్రధానంగా ఇప్ప గింజలు అమ్ముతారు. ఈ సరుకులు అమ్మటం ద్వారా వచ్చిన డబ్బుతో వాళ్ళు బట్టలు, ఇతర అవసరమైన వస్తువులు కొనుక్కుంటారు.

- మీరు ఏఏ అటవీ ఉత్పత్తులు తింటారు? ఒక జాబితా తయారు చెయ్యండి.
- అడవిలో ఏమైన ఆహార ఉత్పత్తులు మీరు సేకరించారా? సేకరించినట్లయితే మీ అనుభవాలను పేర్కొనండి.

5.5 తాగు నీళ్ళు

ఈ గ్రామస్తుల తాగునీటి అవసరాలు తీర్చే ఎన్నో సహజ నీటి ఊటలు ఉన్నాయి. ఇవి కాక కొండల నుంచి ప్రవహించి శబరి లేదా గోదావరి నదిలో కలిసే ఎన్నో వాగులు ఉన్నాయి. రాళ్ళు ఉండటం వల్ల కొండలలో బావులు తవ్వటం చాలా కష్టం నీటి ఊటలలో సంవత్సరం పొడవునా నీళ్ళు లభిస్తాయి,

SCERT, TELANGANA

though some of these natural springs do dry up in summer. Streams are seasonal and last for a few months after the rains. For people in this village, the spring is at a distance of about 30 minutes walk.

Fig. 5.7: Carrying water from the spring

5.6 Bamboo

As we know, bamboo is abundant in the forests. Apart from it being a food source, bamboo is used to build houses, fences etc. People also make baskets, winnows, chicken coops etc. with it and sell them in the Weekly Fairs.

Paper Mills also have the right to collect bamboo from the forest. There are agents who employ people in the village to cut and supply bamboo for the mills. This provides some earning opportunities to them. Initially, the wages were very low but they have increased slowly over the last few years. These wage workers go collect for bamboo after the cropping season. They earn about 150 Rs. per day.

- How is the use of bamboo in tribal life different from that of the paper mill?

5.7 Houses and habitation

We have seen that the houses in Penugolu are mostly built of mud, bamboo and thatch. There is a seperate space to keep the animals and grow vegetables in the kitchen garden around the house. There are fences around the house to protect these crops and animals. Each house is at a little distance from the other.

Houses in Penugolu are at the top of the hills. There were 32 families living here and the total population is 124. These settlements are not permanent. In case, there is an epidemic or any other reason, they can quickly abandon the settlement and build their houses elsewhere.

- What similarities and differences do you think, are there between the settlements in plateaus and hills?

5.8 Customs

The tribal people in Penugolu worship Gods of Nature. The festivals follow the changes in the season. They worship stone idol of Muthyalamma under tamarind tree. They celebrate yellanampadam (bhumi pooja), Kodathala panduga (peddalapanduga),

Fig 5.8 : Hut made of bamboo and thatch



SCERT, TELANGANA

కొన్ని వేసవిలో ఎండిపోతాయి. వానలు అయిపోయిన తరువాత కొన్ని నెలల పాటు వాగులు ప్రవహిస్తాయి. నీటికోసం గ్రామస్తులు 30 నిమిషాలు నడిచి వెళ్ళాల్సి ఉంటుంది.

చిత్రం 5.7: ఊట నుంచి నీళ్ళు తీసుకెళుతున్న ప్రజలు

5.6 వెదురు

ఇంతకు ముందు తెలుసుకున్నట్టు అడవిలో వెదురు దండిగా దొరుకుతుంది. అది వాళ్ళకు ఆహారంగానే కాకుండా ఇళ్ళు, దడులు కట్టుకోటానికి ఉపయోగ పడుతుంది. వెదురుతోటి బుట్టలు, చాటలు, కోళ్ళ గంపలు వంటివి అల్లి సంతలలో అమ్ముతారు.

అడవి నుంచి వెదురు సేకరించే హక్కు పేపరు మిల్లులకు కూడా ఉంది. వెదురు కొట్టించి మిల్లులకు సరఫరా చేసే ఏజెంట్లు ఉంటారు. దీని ద్వారా వాళ్ళు కొంత కూలీ పొందుతారు. మొదట్లో దీనికి చాలా తక్కువ కూలీ లభించేది గత కొద్ది సంవత్సరాలలో ఇది మెల్లగా పెరిగింది. పంటలు అయిపోయిన తరువాత వెదురు కొట్టే పనికి వెళతారు. ఈ పనిద్వారా రోజుకి 150 రూపాయలు సంపాదిస్తారు.

> వెదురును పేపరుమిల్లు ఉపయోగించుకోటానికీ, గిరిజనులు తమ జీవితంలో ఉపయోగించుకోవటానికీ మధ్య తేడాలు చర్చించండి.

5.7 ఇళ్ళు, నివాస ప్రాంతాలు

పెనుగోలులో వెదురు, మట్టి, గడ్డితో ఇళ్ళు కట్టుకుంటారని మనం చూశాం. ఇంటి చుట్టూతా పశువులకు, కూరగాయలు పెంచటానికి స్థలం ఉంటుంది. ఇంటి చుట్టూ ఉండే కంచె పశువులకు, కూరగాయ మొక్క లకు రక్షణగా ఉంటుంది. ఇంటికీ, ఇంటికీ మధ్య కొంచెం దూరం ఉంటుంది.

పెనుగోలులో ఇళ్ళు గుట్టలపైన ఉంటాయి. ఇక్కడ మొత్తం 32 కుటుంబాలు ఉన్నాయి. 124 మంది ఉన్నారు. ఈ నివాస ప్రాంతాలు శాశ్వతమైనవి కావు. ఏవైనా అంటురోగాలు ప్రబలినా, ఇతర కారణాల వల్లా ఈ ప్రాంతాన్ని విడిచిపెట్టి మరొక చోట ఇళ్ళు కట్టుకుంటారు.

> పీఠభూమిలోను, కొండలలో ఉండే నివాస ప్రాంతాలలో పోలికలు, తేడాలు ఏమిటి?

5.8 ఆచారాలు

పెనుగోలు గ్రామస్తులు ప్రకృతి దేవతలను పూజిస్తారు. కాలంలో మార్పులకు అనుగుణంగా పండగలు ఉంటాయి. చింతచెట్టు కింద ఉండే ముత్యాలమ్మ రాతి విగ్రహాన్ని పూజిస్తారు. ఎల్లనంపదం (భూమి పూజ), కొడతల పండగ (పెద్దల పండగ),

చిత్రం 5.8: వెదురు, గడ్డితో చేసిన గుడిసె

SCERT, TELANGANA

Bhimini panduga (festival of vippa poovu). They celebrate Kodathala panduga in September in which they offer vegetables to their deity and then eat them. All major activities like sowing, harvest, collection of fruits from the forest etc. begin after these festivals. During these festivals, all the members of the tribe gather even if they are living in separate settlements.

Fig 5.9 : Gamanu - place of worship

5.9 The Future of Koyas

Even though the hill tribes are very few in number, but they have been following a pattern of life from ancient times. They have a right to their way of life. They do not disturb the environment as compared to modern agriculture. The forests they clear for agriculture are taken care of, so they automatically regenerate after some years. However, with limited forest land available to them now, their way of life is under constant threat. Due to constant felling of trees and over exploitation of bamboo by the paper mills which need daily supply of large quantities of bamboo, the forests are getting depleted. In fact, for a long time the livelihood of tribal people has been repeatedly threatened. The forest officials try to stop the podu cultivation.

- We had discussed about the sustainability of agriculture in the plateau village. Compare the sustainability of livelihoods practiced by the people of the three villages.
- What steps could be taken to ensure that the Koyas have a right to their way of life?

The tribal people possess very intimate knowledge of the fruits of the forest and the forest environment. Considering the fact that the needs of these people are few and the richness of the forests in which they live is immense, it would appear to be in great harmony with nature. Should they not have a right to do so?

School and other such facilities available in the villages are limited. There is just one school, Girijana Primary School. The nearest high school as well hospital are at Wazeed, the Mandal headquarters, that is about 20 k.m. from their village.

SCERT, TELANGANA

Government's Gift for Students' Progress

భీమిని పండగ (ఇప్ప పువ్వు పండగ) వంటి పండుగలు జరువు- కుంటారు. సెప్టెంబరులో కొడతల పండగ చేస్తారు. తమ దేవుడికి కూరలు పెట్టిన తరువాత వాటిని తింటారు. విత్తటం, కొయ్యటం, అడవి నుంచి వేళ్ళు సేకరించటం వంటి ముఖ్యమైన పనులన్నీ పండగ చేసిన తరువాతే మొదలవుతాయి. ఈ పండగలలో వేరు వేరు ప్రాంతాలలో నివసిస్తున్న తెగ సభ్యులందరూ సమావేశం అవుతారు.

చిత్రం 5.9: గమను-పూజలు చేసే చోటు

5.9 కోయల భవిష్యత్తు

ఈ కొండ తెగలు చాలా తక్కువ సంఖ్యలో ఉన్నాయి. అయితే వీళ్ళు చాలా పురాతన కాలం నుంచి తమ జీవన విధానాన్ని కొనసాగిస్తున్నారు. వాళ్ళు జీవన విధానాన్ని కొనసాగించే హక్కు వాళ్ళకు ఉంది. ఆధునిక వ్యవసాయం లాగా వాళ్ళు ప్రకృతిని విధ్వంసం చెయ్యరు. వ్యవసాయం కోసం వాళ్ళు అడవిని నరికే ప్రాంతం కొన్ని సంవత్సరాల తరువాత పునరుద్ధరింపబడేలా వాళ్ళు జాగ్రత్తలు తీసుకుంటారు. అయితే, ప్రస్తుతం వాళ్ళకు చాలా తక్కువ అటవీ ప్రాంతం అందుబాటులో ఉన్నందు వల్ల వాళ్ళ జీవన విధానం దెబ్బతినే ప్రమాదం ఉంది. చెట్లను కొట్టివేస్తూ ఉండటం వల్ల, పేపరు మిల్లులకు ప్రతిరోజు పెద్ద మొత్తంలో కావలసిన వెదురు వల్ల అడవులు క్రమేపీ అంతరించి పోతున్నాయి. చాలా కాలంగా వాళ్ళ జీవనోపాధులు ప్రమాధకర స్థితిలో ఉన్నాయి. పోడు వ్యవసాయాన్ని ఆపటానికి అటవీ అధికారులు ప్రయత్నిస్తున్నారు.

- పీఠభూమి ప్రాంతంలో వ్యవసాయ సుస్థిరత గురించి తెలుసుకున్నారు. ఈ మూడు గ్రామాలలోని ప్రజలు అవలంబిస్తున్న జీవనోపాధుల సుస్థిరతను పోల్చండి.
- తమ జీవన విధానం పై కోయ ప్రజలకు హక్కు ఉండేలా చెయ్యటానికి ఎటువంటి చర్యలు తీసుకోవాలి?

అటవీ పర్యావరణం గురించి, అడవిలో దొరికే పళ్ళ గురించి వాళ్ళకు అపార జ్ఞానముంది. ఈ ప్రజల అవసరాలు చాలా తక్కువ. వాళ్ళు ఉండే అడవులు అపార సంపద కలిగి ఉన్నాయి అని తెలుసుకుంటే వాళ్ళు ప్రకృతిలో ఎంతో సామరస్యంతో జీవిస్తున్నారని అర్థమవుతుంది. అలా జీవించే హక్కు వాళ్ళకు ఉండకూడదా?

ఈ గ్రామంలో బడి, ఇతర సౌకర్యాలు వంటివి, చాలా తక్కువ. ఇక్కడ ఒక గిరిజన ప్రాథమిక పాఠశాల మాత్రమే ఉంది. ఉన్నత పాఠశాల, ఆసుపత్రి సౌకర్యం కోసం 20 కిలోమీటర్ల దూరంలో ఉన్న మండల కేంద్రం వాజేడు దాకా వెళ్ళవలసిందే.

SCERT, TELANGANA

Fig 5.10 : Path way leading to Penugolu village

Keywords

Podu   Tribe   Bamboo   Kitchen garden   Forest products

IMPROVE YOUR LEARNING

1. What are the various ways in which the Koyas are dependent upon the forests around them?
2. List out various means of living in a hill region.
3. Why do the Koyas move from one hill to another for growing crops?
4. Compare the nature of the fields in the three villages that you studied and bring out their similarities and differences.
5. Read the various sub-headings in the last three chapters. Fill the following table with information regarding various aspects of the three villages. (Add more rows if necessary – write "no information" if you cannot find similar headings)

Sub headings/Headings	Hill village	Plateau village	Plain village

6. Your village/town is currently located in _________ type of land form. Imagine that your village is located in a different type of land form and write about it.

E6N9A8

Discussion: What will happen, if there are no trees? Discuss, its effect and our responsibility.

SCERT, TELANGANA

చిత్రం 5.10: పెనుగోలు గ్రామానికి వెళ్ళేదారి

కీలకపదాలు

పోడు　　తెగ　　వెదురు　　పెరటితోట　　అటవీ ఉత్పత్తులు

మీ అభ్యసనాన్ని మెరుగుపరచుకోండి

Z8X9P2

1. తమ చుట్టు పక్కల ఉన్న అడవులపై కోయలు ఏ విధంగా ఆధారపడి ఉన్నారు?
2. కొండ ప్రాంతంలో వివిధ జీవనోపాధులను పేర్కొనండి.
3. కోయలు పంటలు పండించటానికి ఒక చోటు నుంచీ ఇంకొక చోటుకి ఎందుకు మారతారు?
4. మీరు తెలుసుకున్న మూడు గ్రామాలలోని భూముల మధ్య తేడాలను, పోలికలను పేర్కొనండి.
5. గత మూడు అధ్యాయాలలోని ఉపశీర్షికలు చదవండి. ఈ మూడు గ్రామాలలోని వివిధ అంశాలకు సంబంధించిన సమాచారాన్ని కింది పట్టికలో నింపండి. (అవసరమైతే మరిన్ని అడ్డ వరసలు చేర్చండి, ఆ అంశం ఒక ఊరిలో లేకపోతే 'సమాచారం లేదు' అని రాయండి)

ఉపశీర్షిక/శీర్షిక	కొండల మీది గ్రామం	పీఠభూమి ప్రాంత గ్రామం	మైదాన ప్రాంత గ్రామం

6. మీ ఊరు/పట్టణం ఇప్పుడు .... రకం నేల రూపంలో ఉంది. ఇందుకు భిన్నమైన నేల రూపంలోని మీ ఊరు ఉందని ఊహించుకుని దాని గురించి రాయండి.

చర్చ : చెట్లు లేకపోతే ఏమవుతుంది? దాని ప్రభావం, మన బాధ్యతను చర్చించండి.

SCERT, TELANGANA