CHAPTER 20

SCULPTURES AND BUILDINGS

U5B1P7

Archaeologists digging the ancient cities of Indus Valley found some very nice stone and bronze sculptures besides seals carved on stones and baked clay figurines. These were made some 4000 years ago. You can see some of their pictures here. You can see that these depict everything in a natural manner. We don't know what they were used for.

Fig. 20.1: A small bust of a male person of importance – was he a priest or a king?

Fig. 20.3: A bronze statue of a girl standing

Fig. 20.2: A beautiful Harappan Seal showing a bull



Fig. 20.4: A mother goddess figurine of terracotta

SCERT, TELANGANA

అధ్యాయం 20 శిల్పం మరియు కట్టడాలు

W2B2S8

ప్రాచీన సింధులోయ నగరాలలో తవ్వకాలు జరిపిన పురాతత్వ శాస్త్రజ్ఞులు రాతిపైన చెక్కిన ముద్రలను, కాల్చిన బంకమట్టి ఆకృతులతో పాటు అందమైన రాతి, కంచు శిల్పాలను కనుక్కొన్నారు. నాలుగు వేల సంవత్సరాల క్రితం చేసిన చిత్రాలను కొన్నింటిని మీరు ఇక్కడ చూడొచ్చు. ఇవన్నీ సహజసిద్ధమైన అంశాలను ప్రతిబింబిస్తాయి. అయితే, వాటిని ఎందుకోసం ఉపయోగించారో మనకు తెలియదు.

చిత్రం 20.1: సింధులోయ కాలం నాటి ఒక ముఖ్య వ్యక్తి ప్రతిమ, ఇతను పూజారా? లేదా రాజా?

చిత్రం 20.3: నిలబడినట్లున్న ఓ బాలిక కంచు విగ్రహం

చిత్రం 20.2: ఎద్దు బొమ్మ కలిగిన అందమైన హరప్పా ముద్ర

చిత్రం 20.4: టెర్రకోటతో చేసిన అమ్మతల్లి ఆకృతి

SCERT TELANGANA

20.1 Harappan Cities – The first cities of the subcontinent

In chapter 6, you read that humans led a migrant or nomadic life as hunter gathers for a very long time. It was only 10,000 years ago that people began agriculture and animal herding in modern Syria and Palestine. In the Indian sub-continent, some of the earliest villages are found in the North west, in Baluchistan dating from seven to eight thousand years ago. People in different regions took to agriculture and village life very slowly and most people still practiced hunting and gathering. But when did the first cities emerge? In the Indian sub-continent, it happened some 5000 years ago again in the Northwestern parts in Baluchistan, Sindh, Punjab and Gujarat. Archaeologists have excavated remains of large cities. Though we do not know the actual names of those cities, we call them by the modern names of the villages in which the remains have been found. You may have heard of famous cities like Harappa, Mohenjodaro, Kalibangan and Lothal. These are among the most ancient cities of our subcontinent. These cities were spread from Afghanistan in the North to Gujarat in the south and Punjab and Haryana in the east and Baluchistan in the west and had many common features. Archaeologists use a common name "Harappan Culture" to denote this phase of our history. Sometimes, it is also called 'The Indus Valley Civilisation' as most of the important sites of this culture were situated in the plains watered by River Indus and its tributaries.

- Find out the names of rivers that flow in these regions. Locate these
- places on a map and see how far are they from Hyderabad.
- Do you think Telangana was part of the Harappan culture? Would the people living in Telangana have known about the Harappan people? How?
- If you visit a place, how will you decide if it is a village or a town?
- What kind of activities go on in a city that are different from a village?
- How do you think archaeologists figure out from remains of ancient ruins if a place was a village or a city? Can you think of the special features in the remains of a city which will not be there in the remains of a village?

SCERT, TELANGANA

20.1 హరప్పా నగరాలు – ఉపఖండము యొక్క మొట్టమొదటి నగరాలు

మానవులు చాలాకాలం పాటు వేట మరియు ఆహార సేకరణ జరుపుతూ, వలస మరియు సంచార జీవనం గడిపేవారని మీరు 6వ అధ్యాయంలో చదివియున్నారు. కేవలం 10,000 సంవత్సరాల పూర్వం నుండే నవీన సిరియా మరియు పాలస్తీనా వాసులు వ్యవసాయం మరియు జంతువులను మచ్చిక చేసుకోవడం ప్రారంభించారు. భారత ఉపఖండంలో ఏడు నుండి ఎనిమిది వేల సంవత్సరాల నాటి పురాతన గ్రామాలు బెలూచిస్తాన్‌లోని వాయవ్య ప్రాంతంలో బయల్పడ్డాయి. వివిధ ప్రాంతాలలోని ప్రజలు వ్యవసాయం చేస్తూ, గ్రామీణ జీవితాన్ని నెమ్మదిగా స్వీకరించినా, ఇప్పటికి చాలా మంది వేట మరియు ఆహార సేకరణను కొనసాగిస్తున్నారు. మరి, మొట్టమొదటి నగరాలు ఎప్పుడు నిర్మింపబడి ఉంటాయి? సుమారు 5000 సంవత్సరాల క్రితం, భారత ఉపఖండంలోని వాయవ్య ప్రాంతాలైన బెలూచిస్తాన్, సింధ్, పంజాబ్ మరియు గుజరాత్‌లలో ఇవి ఉద్భవించాయి. పురావస్తు శాస్త్రజ్ఞులు తమ త్రవ్వకాలలో పెద్ద పెద్ద నగరాల అవశేషాలను కనుగొన్నారు. ఆ నగరాల అసలు పేర్లు మనకు తెలియకపోయినా, వాటి అవశేషాలు బయల్పడిన ఆధునిక గ్రామాల పేర్లతో వాటిని పిలుస్తాం. మీరు ప్రఖ్యాతిగాంచిన హరప్పా, మొహెంజొదారో, కాళీబంగన్ మరియు లోథాల్ నగరాల పేర్లను వినే ఉంటారు. భారత ఉపఖండంలో పేరుగాంచిన ప్రాచీన నగరాలలో ఇవి ప్రముఖమైనవి. ఈ నగరాలు ఉత్తరాన ఉన్న ఆఫ్ఘనిస్తాన్ నుండి దక్షిణాన ఉన్న గుజరాత్ వరకు మరియు తూర్పున పంజాబ్ మరియు హర్యానాల నుండి పశ్చిమాన బెలూచిస్తాన్ వరకు అనేక ఒకే రకమైన (ఉమ్మడి) లక్షణాలతో విస్తరించబడ్డాయి. చరిత్రలోని ఈ దశను పురావస్తు శాస్త్రజ్ఞులు 'హరప్పా సంస్కృతి' అనే పేరుతో సూచిస్తారు. ఈ సంస్కృతిలోని ముఖ్యమైన ప్రాంతాలలోని అధిక భాగం సింధూనది మరియు దాని ఉపనదులతో ఏర్పడిన మైదాన ప్రాంతాలలో ఉండటం వల్ల కొన్నిసార్లు దీనిని 'సింధూలోయ నాగరికత' అని కూడా పిలుస్తారు.

- ఈ ప్రాంతాలలో ప్రవహించే నదుల పేర్లను కనుగొనండి. ఈ ప్రాంతాలను పటంపై గుర్తించి, అవి హైద్రాబాదు నుండి ఎంత దూరంలో ఉన్నాయో గమనించండి.
- తెలంగాణ హరప్పా సంస్కృతిలో భాగమని మీరు భావిస్తున్నారా? తెలంగాణలో నివసించే ప్రజలకు హరప్పా సంస్కృతి గురించి తెలుసా? ఎట్లు?
- మీరు ఏదైనా ఒక ప్రాంతాన్ని సందర్శిస్తే, అది ఒక గ్రామమా లేదా పట్టణమా అని ఎలా నిర్ణయిస్తారు?
- గ్రామానికి భిన్నంగా ఉండే నగరంలో ఎటువంటి కార్యకలాపాలు నిర్వహింపబడతాయి?
- పురావస్తు శాస్త్రజ్ఞులు ప్రాచీన అవశేషాల ఆధారంగా ఒక ప్రాంతం గ్రామమా లేదా నగరమా అని ఎలా నిర్ణయిస్తారని నీవు అనుకుంటున్నావు? గ్రామ అవశేషాలలో ఉండని ఏ ప్రత్యేక లక్షణాలు నగర అవశేషాలలో ఉంటాయని నీవు భావిస్తావు?

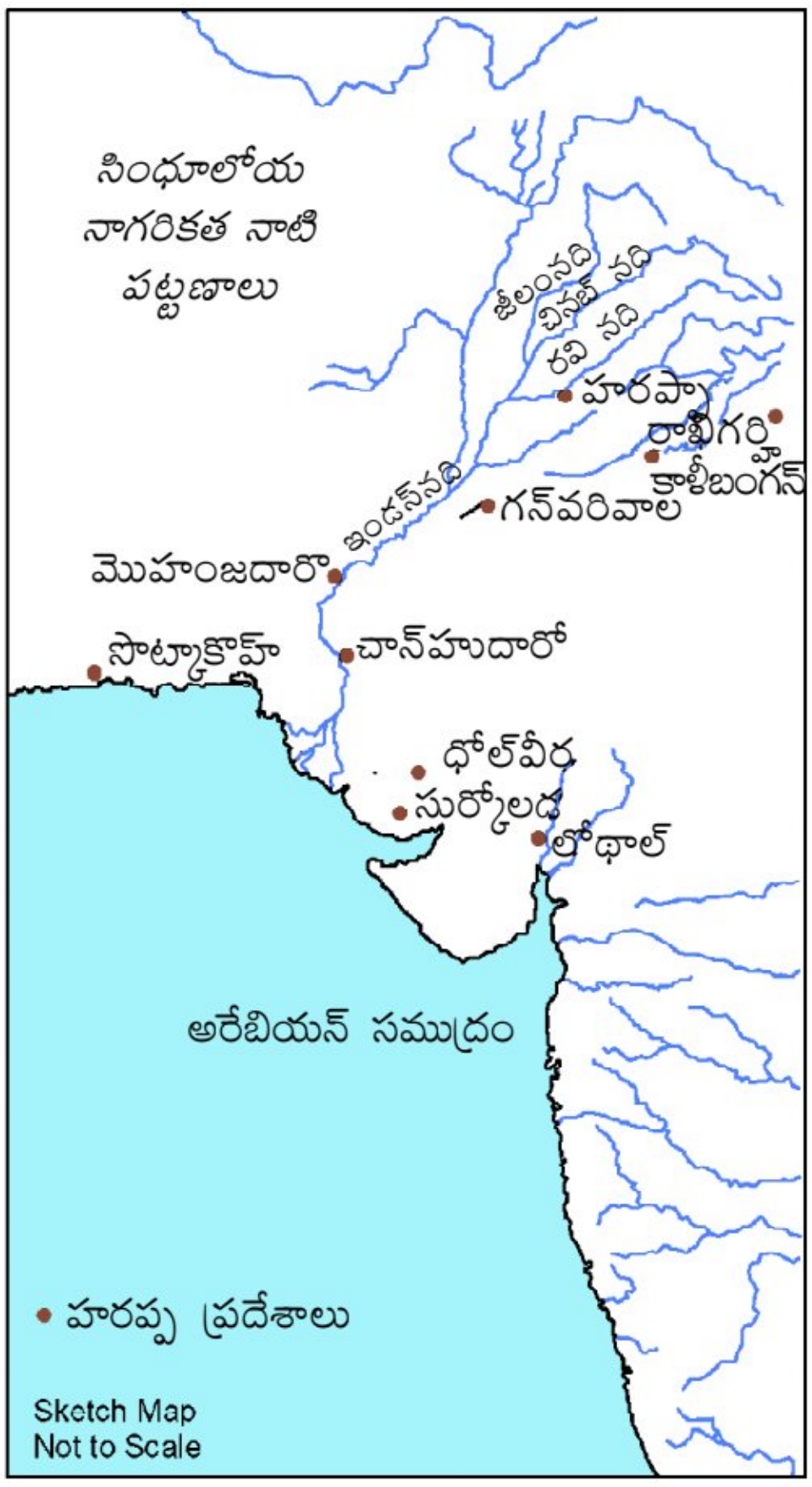

SCERT, TELANGANA

20.1.1 What are cities?

By '*cities*', we mean a place where a large number of people live who do not depend on either agriculture or hunting gathering for their livelihoods. Cities primarily have people from three or four kinds of professions: artisans like potters, metal smiths, carpenters, masons, stone cutters etc.; traders who buy and sell things made by other people both in the city and outside of it; rulers like kings, nobles, priests and administrators; and finally, poor labourers or soldiers who serve others. Most of these people would not cultivate land or grow crops and therefore, depended upon the grains produced by farmers or milk and meat etc. produced by herders. Cities would procure these grains through taxes on the farmers or in exchange for artisanal products. Thus, like today, even in those early times most people probably lived in villages or in forests.

- Do you think the ruins of the houses of rulers and houses of artisans would look similar or different? How ?
- Do you think it is possible to find out if there were traders in a city and where they lived by just studying the ruins?
- Why do you think would the farmers have agreed to give their produce to city dwellers?

20.1.2 Features of the cities

The Harappan cities emerged very rapidly some four thousand six hundred years ago and flourished for about seven hundred years and eventually disappeared about three thousand nine hundred years ago. Buildings in the Harappan cities were built with good baked bricks of a standard size and shape. This is a remarkable feature of these cities. Most of the important cities show carefully planned development of towns as they have a clear lay out with straight roads which intersect each other like in a chess board. The roads had drains to carry dirty water from houses and rain water. Most of the cities were divided into two clear sections, one, a high citadel in which there were some important public buildings like granaries, halls and large buildings; second, a lower part which seemed to have had residential blocks for artisans, traders, and other ordinary people. It appears that the rulers lived or worked in the citadel and wanted to distinguish themselves from the ordinary people.

- Do you see any difference in the lay out of areas where powerful people live or work and where ordinary people live in today's towns? Why is there a difference?

What kind of artisans lived in the Harappan cities? You can guess one kind of artisans from the bricks and buildings – the brick makers or probably potters and masons. Harappan potters produced some of the finest pots made in Indian history, and made a large variety of clay pots and toys. People of Harappan cities extensively used objects made of different kinds of metals like copper, silver, tin etc and mixed metals like bronze.

SCERT, TELANGANA

20.1.1 నగరాలంటే ఏమిటి ?

జీవనోపాధికోసం వ్యవసాయం లేదా వేట మరియు ఆహార సేకరణలపై ఆధారపడకుండా జీవించే అధిక జనాభా కలిగిన ప్రాంతాలను 'నగరాలు' అని మనం అంటాము. నగరాలు ముఖ్యంగా మూడు లేదా నాలుగు రకాల ప్రజలను కలిగి ఉంటాయి. ఉదా॥ చేతివృత్తుల వారు–కుండల తయారీదార్లు, లోహపు పనివారు, వడ్రంగి పనిచేసే వారు, భవన నిర్మాణం చేసే మేస్త్రీలు, రాళ్ళను కొట్టేవారు, మొదలైనవారు; వర్తకులు–నగరం లోపల మరియు బయట ఉండేవారు తయారు చేసిన వస్తువులను కొనడం లేదా అమ్మడం చేసే వ్యాపారులు; పరిపాలకులైన రాజులు, కులీనులు, పూజారులు మరియు పరిపాలనాధికారులు; చివరగా పేద శ్రామికులు లేదా సైనికులు వీరు ఇతరులకు సేవ చేసేవారు. వీరిలో చాలా మంది వ్యవసాయం చేయరు లేదా పంటలను పండించరు. అందువలన ధాన్యము ఉత్పత్తి చేసే రైతులపై, పాలు మరియు మాంసం ఉత్పత్తి చేసే పశుపోషకులపై ఆధారపడతారు. నగరాలు ఈ ధాన్యాలను రైతులపై విధించే పన్నుల ద్వారా లేదా చేతిపనుల ద్వారా వచ్చే ఉత్పత్తులకు బదులుగా పొందుతాయి. నేడు ఉన్న పరిస్థితులలాగానే ఆ ప్రాచీన యుగంలో కూడా అధిక శాతం మంది ప్రజలు బహుశా గ్రామాలలోనో లేదా అడవులలోనో నివసించి ఉండవచ్చు.

- పరిపాలకుల మరియు పనివారి శిధిల భవనాలు ఒకేలాగా ఉన్నాయా? విభిన్నంగా ఉన్నాయా? ఎలా?
- కేవలం శిధిలాలను అధ్యయనం చేసి, ఆకాలంలో వర్తకులున్నారో లేదో, వారి నివాస ప్రాంతాలు ఎక్కడున్నాయో తెలుపడం సాధ్యమని మీరు అనుకుంటున్నారా?
- రైతులు తమ ఉత్పత్తిని నగరవాసులకు ఇవ్వడానికి ఎందుకు ఒప్పుకున్నారని మీరు భావిస్తున్నారు?

20.1.2 నగరాల లక్షణాలు

సుమారు నాలుగువేల ఆరు వందల సంవత్సరాల క్రితం హరప్పా నగరాలు వేగంగా ఏర్పడి దాదాపు ఏడు వందల సంవత్సరాలు వెలుగొందాయి. సుమారు మూడువేల తొమ్మిది వందల సంవత్సరాలలో క్రమేణ కనుమరుగయ్యాయి. హరప్పా నగరాలలోని భవనాలు బాగా కాల్చిన, నిర్ణీత ఆకారము, పరిమాణము గల ఇటుకలతో నిర్మించబడటం ఆ నగరాల ఒక విశిష్ట లక్షణం. దాదాపు అన్ని ప్రముఖ నగరాలు జాగ్రత్తగా రూపొందించిన ప్రణాళికాబద్ధమైన పట్టణాభివృద్ధిని కలిగి, చదరంగంలోని గడులవలె ఒకదానినొకటి ఖండించుకుంటున్న వంకరలు లేని రహదార్లతో నిర్మించబడ్డాయి. రహదారులన్నీ గృహాల నుండి వచ్చే మురుగు నీటి పారుదల, వర్షపునీటి పారుదల కోసం చక్కటి కాలువలతో నిర్మించబడ్డాయి. దాదాపు అన్నీ నగరాలు రెండుగా విభజింపబడి నిర్మించబడ్డాయి. ఒక భాగంలో ఎత్తైన భవనాలు, ప్రధాన రాజ ప్రాసాదాలు (కోటలు), నివాసాలు, కార్యాలయాలు, ధాన్యా గారాలతో ఉండగా, మరియొక భాగంలో చేతి వృత్తులు, వర్తకులు మరియు ఇతర సామాన్య ప్రజల నివాసాలుండేవి. పరిపాలకులు రాజ ప్రాసాదాలలో నివసిస్తూ పని చేస్తూ, ఇతర సామాన్య ప్రజల నుండి విడిగా ఉంటూ తమ ప్రత్యేకతను చాటుకుంటూ ఉండేవారు.

- నేటి పట్టణాలలో స్థితిమంతులైన ప్రజలు నివసించే ప్రాంతాలు లేదా పనిచేసే స్థలాలకును సామాన్య ప్రజల నివాస ప్రాంతాలకును మధ్యన మీరు ఏవైనా తేడాలు గమనించారా? ఈ తేడాలు ఎందుకున్నాయి?

హరప్పా నగరాలలో ఎటువంటి చేతి వృత్తుల వారు నివసించేవారు? భవనాలు, అవి నిర్మింపబడిన ఇటుకల ప్రాముఖ్యతను బట్టి చేతి వృత్తుల పనివారిలో ఒక రకాన్ని మీరు ఊహించవచ్చు – ఇటుక తయారీదారులు లేదా భవననిర్మాణ మేస్త్రీలు లేదా మట్టితో పనిచేసే కుండల తయారీదారులు. హరప్పా కాలం నాటి కుండల తయారీదారులు భారత చరిత్రలోనే అత్యంత నాణ్యతగల కుండలను, విభిన్న రకాల మట్టి పాత్రలను, బొమ్మలను తయారు చేసేవారు. హరప్పా ప్రజలు వివిధ రకాల లోహాలతో తయారైన అనగా రాగి, వెండి, తగరం, మిశ్రలోహమైన ఇత్తడి మొదలైన వాటితో తయారయిన వస్తువులను విస్తృతంగా ఉపయోగించేవారు.

SCERT, TELANGANA

Fig. 20.5: Dockyard of Lothal - Imagine, the size of the boat that can fit here.(Dimensions 37m east-west, 22m north-south)

However, they did not use iron which came into use in India much later. Copper being a rare metal had limited use. Harappans continued to use stone and wood for most of their daily needs. They used very fine and long stone blades for cutting, finely carved stone seals for trading, beautiful and colourful polished stone beads for ornaments, and stone weights and measures for trading. They wove cotton and woollen clothes and some small fragments of these have survived. They also used sea shells to make objects of daily use like ladles, spoons and bangles.

The use of seals and weights indicate that the Harappan cities had a large number of traders who took merchandise from one place to another. In fact, they also went by ships to trade in distant lands like Iraq where too many cities had developed. They must have used bullock carts and boats to transport their goods.

- Do you think that the same artisans can make all these goods or different artisans were needed for making different kinds of things? Why do you think so?

201.3 Language

We do not have any books written by the Harappan people; we do have some small inscriptions on seals etc. but we don't know how to read them. Hence, we do not know what language they spoke and if they spoke any common language at all. We also don't know what names



Fig. 20.6: Citadel of Mohenjodaro

SCERT, TELANGANA

చిత్రం 20.5: లోథల్ నౌకానిర్మాణ కేంద్రం-ఇక్కడ సరిపోయే నావ పరిమాణాన్ని ఊహించండి (కొలతలు: తూర్పు-పడమరల మధ్యం దూరం -37మీ, ఉత్తర-దక్షిణాల మధ్య దూరం-22మీ.)

అయినా, భారతదేశంలో ఆలస్యంగా వాడుకలోనికి వచ్చిన ఇనుమును వీరు ఉపయోగించలేదు. రాగి అరుదుగా లభించేది దాని ఉపయోగం పరిమితిగా ఉండేది. హరప్పా ప్రజలు తమ నిత్యావసరాల కోసం రాయి మరియు చెక్కతో చేసిన పనిముట్లను ఎక్కువగా ఉపయోగించేవారు. నరికేపని కోసం రాతితో చేయబడిన పొడవుగా ఉండే విశిష్టమైన రంపాలను, వర్తకం కోసం చక్కగా చెక్కబడని రాతి ముద్రలను, ఆభరణాల కోసం అందమైన, రంగులతో నునుపుగా తయారు చేసిన రాతి పూసలను, వ్యాపారం కోసం రాతిబాట్లను (బరువును సూచించే రాళ్ళు) ఉపయోగించేవారు. పత్తి, ఉన్ని బట్టలను తయారు చేసేవారు. వీటిలో చాలా తక్కువ పరిమాణంలో కొన్ని చరిత్రకారులకి లభ్యమయ్యాయి. ప్రతిరోజూ ఉపయోగించే వస్తువులైన గరిటెలు, కాడలు, గాజులను తయారు చేయడానికి సముద్రంలో లభ్యమయ్యే గవ్వలు, శంఖాలను ఉపయోగించేవారు.

రాతిముద్రలు, బరువుల (తూనిక బాట్లు) ఉపయోగాన్ని గమనిస్తే, ఆ కాలంలో వివిధ ప్రదేశాల మధ్య వర్తక వ్యాపారాలు అధిక సంఖ్యలో జరిగేవని తెలుస్తుంది. నిజానికి, వారు ఎన్నో అభివృద్ధి చెందిన నగరాలు కలిగిన ఇరాక్ లాంటి సుదూరదేశాలకు ఓడలపై ప్రయాణించి వర్తక వ్యాపారాలు కొనసాగించేవారు. సరుకుల రవాణాకు ఎద్దుల బండి మరియు పడవలను వారు తప్పకుండా ఉపయోగించి ఉంటారు.

- ఈ వస్తువులన్నీ ఒకే పనివారు చేస్తుంటారా? లేదా వివిధ వృత్తిపనివారు చేస్తుంటారా? ఈ విధంగా మీరు ఎందుకు భావిస్తున్నారు?

20.1.3 భాష

హరప్పా ప్రజలు రాసిన పుస్తకాలేవి మనకు లభించలేదు. కొన్ని చిన్న శిలాఫలకాలు, ముద్రలు మాత్రము లభించినప్పటికీ వాటిని ఎలా చదవాలో మనకు నేటికి తెలియదు. వారు ఏ భాషను మాట్లాడారో, అన్ని చోట్ల ఒకే భాషను మాట్లాడారా

చిత్రం 20.6: మొహెంజొదారో దుర్గం

SCERT, TELANGANA



Fig. 20.7: Great Bath of Mohenjodaro (Dimensions 11.8x7metres)

they called themselves, or their rulers and gods and even their cities. You will also read about their religious beliefs in a later chapter.

20.1.4 Rulers

We don't know who ruled these cities. Since most of the cities were spread over such a large area and had so many features in common, it has been suggested by some that there must have been one central authority regulating all these things. However, was it a king or a priest or a group of elected leaders, we do not know. They probably lived in the citadels and regulated the life of all city-dwellers from there.

20.1.5 Change in livelihood

It appears that some seven hundred years after the great Harappan cities developed, the towns declined. Trade and artisanal production declined and people moved out of these cities to villages.

In fact, some historians believe that many rivers which flowed through this area dried up and people shifted further eastwards towards Ganga river. They mingled with other farming and herding people. However, the great cities of the Harappan culture gradually disappeared forever, to be buried under mud. They were discovered in the early twentieth century when archaeologists began a systematic study of this lost civilisation.

- Do you know of people who have changed their livelihood – from being farmers to factory workers or office workers or shopkeepers? Or factory workers who take to odd jobs in the market? Or people who have to leave their ancestral place and go to new places in search of work? Describe their life and the problems and challenges faced by them.

Fig. 20.8: Drianage system in a street in Mohenjodaro

SCERT, TELANGANA

చిత్రం 20.7: మొహెంజాదారో మహాస్నాన ఘట్టం (కొలతలు : 11.8మీ × 7 మీ)

అన్న విషయం కూడా తెలియదు. వారు ఏయే పేర్లతో పిలుచుకున్నారని గాని, రాజులను, దేవుళ్ళను ఎలా పిలిచారో గాని, చివరికి వారి నగరాల పేర్లు కూడా తెలియదు. వారి మత విశ్వాసాలను గురించి మీరు తర్వాత పాఠంలో చదువుతారు.

20.1.4 పాలకులు

ఈ నగరాలను ఎవరు పరిపాలించారో తెలియదు. నగరాలు చాలా విశాల ప్రాంతాలలో నిర్మాణం అయివున్నాయి. దాదాపు అన్ని నగరాలలోను సాధారణంగా ఉండే అంశాలు ఒకే రకంగా ఉండటంచే, కొంతమంది అభిప్రాయం ప్రకారం వీటిని అజమాయిషీ చేయడానికి ఒక కేంద్రీకృత వ్యవస్థ ఉండేదని తెలుస్తుంది. ఈ కేంద్రీకృత వ్యవస్థను రాజు, పుజారి లేదా ఎన్నుకోబడిన కొంత మంది నాయకులు వీరిలో ఎవరు అజమాయిషీ చేసారో తెలియలేదు. బహుశా వారు పెద్ద పెద్ద కోటలలో నివసిస్తూ, నగర ప్రజలను పరిపాలించి ఉండవచ్చు.

20.1.5 జీవనోపాధిలో మార్పు

దాదాపు ఏడు వందల సంవత్సరాల తరువాత గొప్ప నగరాలుగా అభివృద్ధి చెందిన పట్టణాలు, వర్తకం, చేతి వృత్తుల వారి ఉత్పత్తి తగ్గిపోయి, క్రమేణ క్షీణించి, ఇక్కడి ప్రజలు పట్టణాల నుండి గ్రామాలకు తరలి వెళ్లారు.

కొంత మంది చరిత్రకారుల అభిప్రాయం ప్రకారం ఈ ప్రాంతంలో ప్రవహించే చాలా నదులు ఎండిపోవడంచే, ఇక్కడి ప్రజలు తూర్పుగా గంగానదివైపుకు తరలిపోయారు. అక్కడ వారు వ్యవసాయ, పశుపోషకులతో కలిసిపోయారు. ఏది ఏమైనప్పటికి హరప్పా సంస్కృతిలోని గొప్ప నగరాలు కనుమరుగై, భూమిలో కలిసిపోయారు. అంతరించిపోయిన ఈ నాగరికత గురించి పురావస్తు శాస్త్రజ్ఞులు ఇరవైవ శతాబ్దంలో కనుగొని క్రమబద్ధమైన అధ్యయనం చేయడం మొదలుపెట్టారు.

◆రైతులుగా ఉంటూ కర్మాగార కార్మికులుగా లేదా కార్యాలయ పనివారుగా లేదా దుకాణదారులుగా నీకు తెలిసిన వారు ఎవరైన తమ జీవనోపాధిని మార్చుకున్నారా? లేదా కర్మాగార కార్మికులు ఎవరైనా మార్కెట్‌లో చిన్న చిన్న పనులు చేసే వారిగా మారారా? లేదా తమ పూర్వీకుల ప్రాంతాన్ని వదిలి పెట్టి ఉపాధికోసం కొత్త ప్రదేశాలకు వెళ్లారా? వారి జీవితాలను మరియు వారు ఎదుర్కొనే సమస్యలను, సవాళ్లను వర్ణించండి?

చిత్రం 20.8: మొహెంజాదారో వీధిలోని మురుగు నీరు పారుదల వ్యవస్థ

SCERT, TELANGANA

20.2 Sculpture after Indus Valley Civilisation

A little later, the art of casting metal figures spread to Maharashtra. Some very exquisite bronze figures were found during digging. These were probably made some 3000 years ago. Do you think they could have been toys?

Fig: 20. 9. Daimabad Bronzes

The next important phase of sculpture belongs to the Mauryan period, that is around 2200 years ago. King Ashoka set up some tall, smoothly polished pillars in many places. They were usually made of one piece of stone. Ashoka's messages were carved on them. They also had some figures of animals at their top. These are called capitals. The most famous among them is the Lion Capital of Sarnath set up by Ashoka in the place where Buddha first preached his teachings. These four majestic lions facing the four directions hold the Wheel of Dharma on their pedestal.

- Do you feel that the lions look natural or do they look artificial, posing for the sculpture?
- You must have seen these often. Where do you see pictures of these lions?

These pillars and the Lion Capital represent the power and majesty of the Mauryan emperors. Compare this capital with the Bull capital in Rampurva. Here you can see that the bull looks more natural and quite similar to the Harappan seal's bull.

Fig. 20.10: Sarnath Lion Capital

Fig. 20.11: Rampurva Bull

SCERT, TELANGANA

20.2 సింధూ లోయ నాగరికత తరువాత కాలం శిల్పకళ

కొద్దికాలం తరవాత ఖనిజాలతో ఆకృతులను పోతపోయడం మహారాష్ట్రకు విస్తరించింది. అద్భుతమైన కంచు పోతబొమ్మలు తవ్వకాలలో బయటపడ్డాయి. బహుశా అవి మూడువేల సంవత్సరాలకు పూర్వం పోతపోసినవి అయి ఉండొచ్చు. అవి ఆట బొమ్మలు కూడా అయి ఉండవచ్చునని మీకు అనిపిస్తోందా?

చిత్రం 20.9: దయిమాబాద్ కంచు పోతబొమ్మలు

శిల్పానికి సంబంధించి ముఖ్యమైన తరవాత ఘట్టం 2200 సంవత్సరాల క్రితం నాటి మౌర్యుల కాలం. అశోక చక్రవర్తి అనేక ప్రాంతాలలో బాగా పొడవైన నునుపుదేలిన స్తంభాలను పాతించాడు. వీటిని ఒకే రాతిలో చెక్కారు. వీటిపైన అశోకుని సందేశాలను చెక్కేవారు. ఈ స్తంభాల చివరి భాగాన కొన్ని జంతువుల ఆకృతులు కూడా ఉండేవి. వీటిని రాజచిహ్నాలు (కాపిటల్స్) అంటారు. వీటిలో ప్రముఖమైనది బుద్ధుడు మొదటిసారిగా బోధించిన సారనాథ్‌లోని సింహ శిఖరం. దీన్ని అశోకుడు స్థాపించాడు. రాజసం ఉట్టిపడే ఈ నాలుగు సింహాల తలలు నాలుగు దిక్కులను సూచిస్తూ 'ధర్మచక్రాన్ని' చూపిస్తూ ఉన్నాయి.

- శిల్పంలోని సింహాలు చూడటానికి సహజంగా లేక కృత్రిమంగా కనిపిస్తున్నాయని మీరు భావిస్తున్నారా?
- తరచుగా చూసే సింహాల బొమ్మలను వేటిమీద చూశారు?

ఈ రాతి స్తంభాలు, సింహశిఖరం మౌర్యచక్రవర్తుల శక్తికి, రాజసానికి ప్రతీకలు. ఈ సింహశిఖరాన్ని రాంపూర్వాలోని వృషభ శిఖరంతో పోల్చండి – ఈ ఎద్దు, హరప్పాలోని ఎద్దును పోలి ఎంతో సహజంగా కనిపిస్తోంది కదా!

చిత్రం 20.10: సారనాథ్‌లోని సింహశిఖరం

చిత్రం 20.11: రాంపూర్వలోని వృషభ శిఖరం

SCERT, TELANGANA

20.2.1 Buddhist Stupas and Viharas

Given below is the picture of one of the most famous stupas in India – the Sanchi Stupa. Look at the photo. You can see that it is like a hemisphere (half ball) – just the way the sky looks when you look up.

A stupa is built on a platform. In the centre of a stupa relics of Buddha or other important monks (relics are remains of the body like teeth, bone, hair etc) were buried. The hemisphere is fully packed and you cannot enter it like a temple. Above it there is a pillar topped by umbrella. The stupa is usually surrounded by a stone fence with decorated gateways. Initially, in Ashoka's times they were built with mud, brick and wood but later they were made with stones.

The stupa has many meanings – it is supposed to represent the Buddha. At the same time, it is believed that the dome of the stupa represents the universe and the central pillar being the axis around which the earth revolves and which connects the world below, the earth and the heavens. Pilgrims worship the stupa by offering flowers etc., and going round it in *pradakshina* and meditating in front of it.

- Can you compare a stupa with a temple and point out the similarities and differences between them and how do people worship them?

Fig. 20.12: Sanchi stupa in Madhya Pradesh. It is one of the most important stupas built by King Ashoka. Can you identify the hemisphere, the platform, the umbrella and the fence?

SCERT TELANGANA

20.2.1 బౌద్ధస్థూపాలు, విహారాలు

భారతదేశంలో ప్రఖ్యాతిపొందిన సాంచీ స్థూపపు చిత్రం దిగువన ఉంది. ఒకసారి చిత్రాన్ని చూడండి. మనం ఆకాశంవైపు చూసినపుడు ఎలా కనిపిస్తుందో అదేవిధంగా అర్ధగోళం (సగం బంతి)లా ఈ స్థూపం కనిపిస్తుంది.

ఒక వేదికపైన నిర్మించిన అర్ధగోళపు ఆకారమే స్థూపం. దీని మధ్యలో బుద్ధుడు లేక బౌద్ధ భిక్షువు అవశేషాలు (దంతం, ఎముక, జుట్టు వంటి శరీర భాగాలు) ఉంటాయి. ఈ అర్ధగోళం పూర్తిగా మూసి ఉంటుంది. దీని లోపలికి మనం గుడిలోకి ప్రవేశించినట్లు ప్రవేశించలేం. దీనిపైన ఒక స్తంభం, దాని చివర ఛత్రం ఉంటాయి. చుట్టూ అందంగా అలంకరించిన ముఖద్వారాలు ఉన్న రాతి ప్రహరీ ఉంటుంది. అశోకుని కాలంలో వీటిని మట్టి, ఇటుక, చెక్కతో నిర్మించేవారు. తరవాత రాతితో నిర్మించేవారు.

స్థూపానికి అనేక అర్థాలున్నాయి. దీన్ని బుద్ధునికి ప్రతీకగా భావిస్తారు. అలాగే స్థూపపు గుమ్మటాన్ని విశ్వంగాను, ఈ స్తంభాన్ని భూమిని, స్వర్గాన్నీ కలిపే వారధిగాను భావిస్తారు. యాత్రికులు పుష్పాలతో దీన్ని పూజిస్తారు. దాని చుట్టూ ప్రదక్షిణలు చేస్తారు. స్థూపానికి వెలుపలి వైపు ధ్యానం చేస్తారు.

- స్థూపానికీ, దేవాలయానికీ పోలికలను, తేడాలను పేర్కొనండి. వీటిని ప్రజలు ఎలా పూజిస్తారో చెప్పండి.

చిత్రం 20.132 మధ్యప్రదేశ్‌లో ఉన్న సాంచీ స్థూపం. అశోకుడు నిర్మించిన అత్యంత ప్రాముఖ్యమున్న స్తూపమిది. ఈ చిత్రంలో అర్ధగోళాన్ని, వేదికను, ఛత్రాన్ని, ప్రహరీని గుర్తించండి.

SCERT TELANGANA

Fig. 20.13: *Bhuddist Stupa from Nelakondapally, Khammam District. Can you identify nicely stacked bricks?*

Fig. 20.14: Amaravathi stupa in Andhra Pradesh

Archeologists have found remains of stupas from very early times in several places in Andhra Pradesh like Amaravati, Bhattiprolu, Ramatirtham, Salihundam etc. A crystal casket containing the relics of the Buddha was found at Bhattiprolu Stupa.

Amaravati Stupa in Guntur district is the most famous one in Andhra Pradesh. This was built during the rule of Satavahanas about 1900 years ago.

Fig.20.15 shows a sculpture panel depicting the stupa. Can you see some flying figures on the top? These are supposed to be gods from heavens who came to worship the Buddha. At the bottom, you can see some men and women bowing down and worshipping. You can also see the four lions on the gateway. What do you think they signify?

Today, the Amaravathi stupa is just a mound of rubble. All that we can do is imagine how this great stupa was in the past. The panels help us to imagine how it must have looked 1900 years ago. As you can see from the picture, the stupa was covered with panels of sculptures depicting the Buddha and his teachings. These panels were found by the British and were taken away to London. Some of the panels that could not be transported were kept in Madras Museum. Based on these panels, people have tried to imagine how the stupa would have looked. See the picture of reconstruction and compare it with the panel.

Another important stupa was the Nagarjunakonda stupa. It was a part of Vijayapuri, the capital city of Ikshvaku kings. It was situated on the banks of Krishna River. Vijayapuri had a large number of stupas, *viharas* and palaces. It also had a beautifully designed amphitheatre and ghats leading to the river. Unfortunately, today the entire city

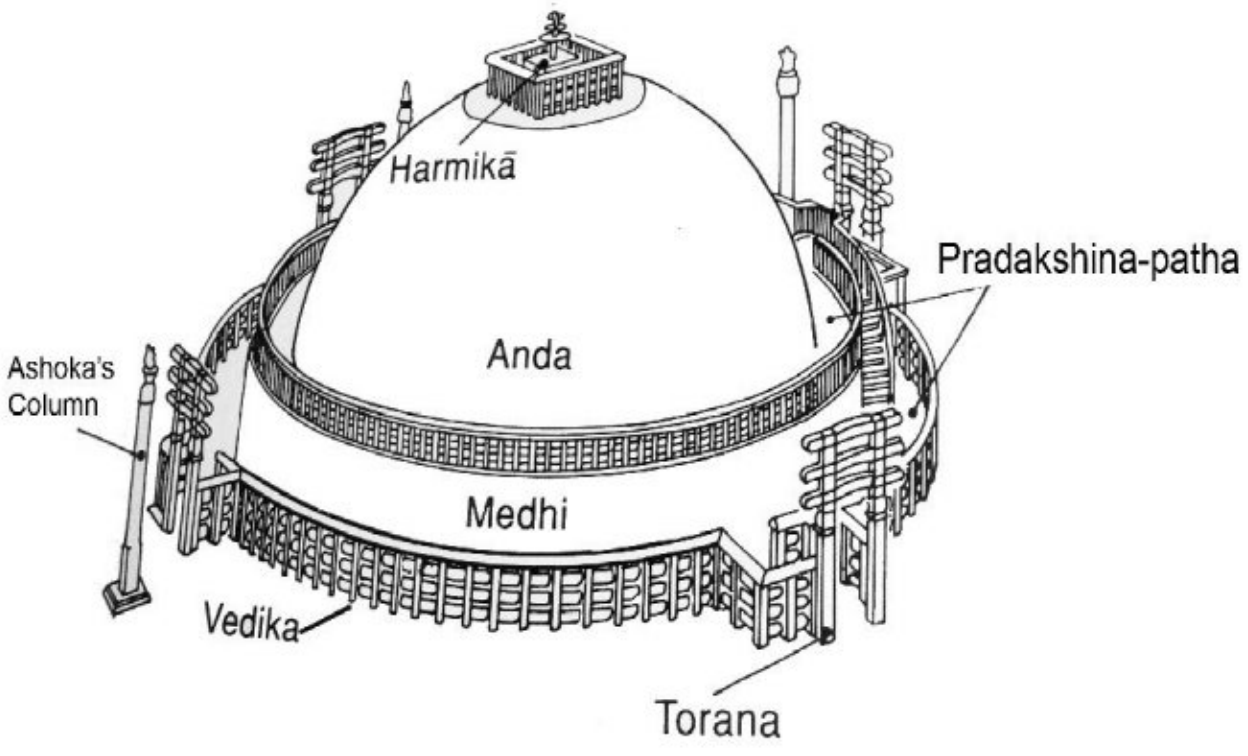

Plan of stupa

Fig. 20.15: Reconstruction of Amaravathi stupa

SCERT, TELANGANA

ఆంధ్రప్రదేశ్‌లోని చాలా ప్రాంతాలలో ముఖ్యంగా అమరావతి, భట్టిప్రోలు, రామతీర్థం, సాలిహుండం మొదలైన ప్రదేశాల్లో పురాతత్వ శాస్త్రజ్ఞులు అనేక ప్రాచీన స్థూప శిథిలాలను కనుక్కొన్నారు. భట్టిప్రోలు వద్ద బుద్ధుని అస్థిక కలిగిన ఒక స్ఫటిక పేటికను కనుక్కొన్నారు.

చిత్రం 20.13: నేలకొండపల్లిలోని బుద్ధ స్థూపం, ఖమ్మం జిల్లా. చక్కగా అమర్చిన ఇటుకలను గుర్తించారా?

చిత్రం 20.14: అమరావతి స్థూపం

ఆంధ్రప్రదేశ్‌లోని గుంటూరు జిల్లాలో ఉన్న అమరావతి స్థూపం అత్యంత ప్రసిద్ధమైనది. 1900 సంవత్సరాలకు పూర్వం శాతవాహనుల కాలంలో దీన్ని నిర్మించారు.

చిత్రం 20.15 శిల్పకళతో కూడిన స్థూపాన్ని వర్ణిస్తుంది. పై భాగంలో కొన్ని ఎగిరే ఆకృతులను చూశారా? బుద్ధున్ని పూజించేందుకు స్వర్గము నుండి దిగి వచ్చిన దేవతలుగా వీరిని భావిస్తారు. దిగువ భాగంలో కొద్దిమంది స్త్రీ, పురుషులు అణకువగా పూజిస్తున్నట్లుంది. ముఖ ద్వారం దగ్గర నాలుగు సింహాలను చూడవచ్చు. ఇవి ఏ అంశాన్ని స్ఫురింప చేస్తాయి?

అమరావతి నేడు చిన్నాభిన్నమైన రాళ్ళతో కూడిన గుట్ట. ఇది 1900 సంవత్సరాల క్రితం శిల్పతోరణాలతో ఎంత అద్భుతంగా ఉండేదో ఊహించుకోవాల్సిందే. బుద్ధుడు, అతని బోధనల గురించి ఈ శిల్ప తోరణాలు తెలియచేస్తాయి. వీటిని బ్రిటిషువారు కనుక్కొని లండన్‌కు తరలించారు. తరలించలేనివాటిని మద్రాసు మ్యూజియంలో భద్రపరిచారు. ఈ తోరణాల స్థూపం ఏవిధంగా ఉండేదో అంచనావేస్తున్నారు. దీని పునర్నిర్మాణం ఈ తోరణాల ఆధారంగా జరిగింది. వాటిని సరిపోల్చండి.

నాగార్జునకొండ స్థూపం మరొక ముఖ్య స్థూపం. ఇక్ష్వాకుల రాజధాని అయిన విజయపురిలో ఇదొక భాగం. కృష్ణానది ఒడ్డున ఇది ఉంది. విజయపురిలో అనేక స్థూపాలు, విహారాలు, రాజప్రాసాదాలు ఉన్నాయి. అందమైన క్రీడాప్రాంగణాన్ని (స్టేడియమ్‌ను) పోలిన నిర్మాణం, నదీ స్నానఘట్టాలు ఉన్నాయి. దురదృష్టవశాత్తూ మొత్తం నగరం

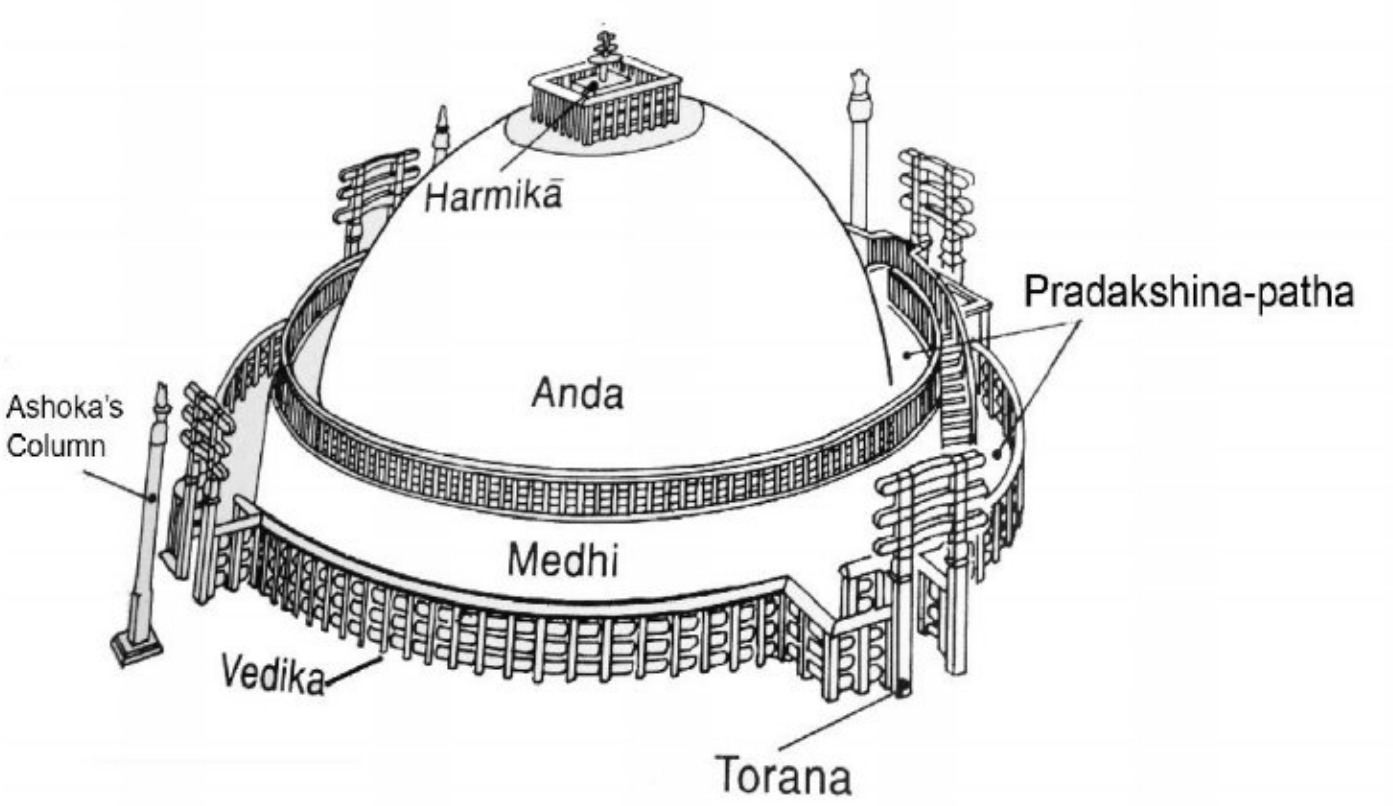

చిత్రం 20.15: అమరావతి స్థూప పునర్నిర్మాణ నమూనా

SCERT, TELANGANA

lies under water – submerged in the Nagarjunasagar dam. A large number of sculptures and other remains have been removed and kept in a museum nearby.

Look at some of the sculpture panels from Nagarjunakonda and Amaravati given below. These sculpture panels represent the earliest sculptural activity in South India. You can get a glimpse of the lives people of those times from them.

As time went on, sculptors started making large and complete figures instead of just the reliefs shown above. Large statues of the Buddha gave people an idea of the peaceful, calm and serene personality of the Buddha. The most famous sculptures of the Buddha come from Gandhara in the Northwest, Mathura and Saranath in Uttar Pradesh (Fig: 17.11). We can see some of these sculptures in Nagarjunakonda too.

Fig. 20.16: A panel from Amaravati showing the calming of an elephant (Nalagiri) by the Buddha. The royal elephant went out of control and the people on the street were panic stricken. However, on seeing the Buddha, the elephant calmed down and bowed down to him. Do you notice how they have shown a story in a panel? What could be the message of the story?

Fig. 20.17: A panel from Nagarjunakonda showing the admission of six princes and the barber Upali into the Sangha. In order to teach humility to the princes, the Buddha admitted Upali first and the rest after him. You can see Upali seated on a low stool besides the Buddha

Fig. 20.18: Panel from Sanchi shows the daily life of villagers. It is a beautiful panel and shows the visit of the Buddha to a village. Can you make a list of activities being done by the people in this panel? Do you get to see similar scenes in today's villages?

Viharas were the monasteries or living places of Buddhist monks where religious education was imparted. A vihara usually had small rooms around an open courtyard and had a small shrine containing a stupa or an image of the Buddha at one end. This shrine was called a *chaitya, which* was also a prayer hall for the monks.

There are cave viharas excavated on hill sides like in Nasik and Karle. These too have some beautiful sculptures carved on them.

SCERT TELANGANA

నాగార్జునసాగర్ నీటిలో మునిగిపోయింది. చాలా శిల్పాలను, అవశేషాలను అక్కడి నుండి తొలగించి దగ్గరలోని మ్యూజియంలో పొందుపరచారు.

కింద ఉన్న నాగార్జునకొండ, అమరావతిలోని శిల్ప తోరణాలలోని భాగాలను చూడండి. దక్షిణ భారతదేశం లోని ప్రాచీన శిల్ప నిర్మితులకు ఇవి ప్రతీకలు. వీటినిబట్టి అప్పటి ప్రజల రూపాలను మలచిన రీతిని గమనించండి.

కాలక్రమంలో శిల్పులు, ఇక్కడ కనిపిస్తున్న ఇలాంటి శిల్ప ఖండికలలో కనిపించే ఆకృతులను మాత్రమే కాకుండా సంపూర్ణమైన పెద్ద ఆకృతులను చెక్కడం ప్రారంభించారు. బుద్ధుని పెద్ద ప్రతిమలు ప్రశాంతమైన, పవిత్రమైన బుద్ధుని వ్యక్తిత్వాన్ని ప్రజలకు చూపించాయి. ప్రఖ్యాత బౌద్ధశిల్పాలు వాయువ్య దిశలోని గాంధారనుంచి ఉత్తర ప్రదేశ్‌లోని మధుర, సారనాథ్ నుంచి లభించాయి. ఇలాంటి శిల్పాలను నాగార్జున కొండలో కూడా చూడవచ్చు.

చిత్రం 20.17: అమరావతిలోని శిల్పసంపద

పిచ్చిపట్టిన నలగిరి అనే ఏనుగును బుద్ధుడు శాంతింప చేయటాన్ని ఈ చిత్రం చూపిస్తుంది. రాజుగారి ఈ ఏనుగు అదుపు తప్పి చెలరేగటంతో వీధుల్లోని ప్రజలు భయభ్రాంతులయ్యారు. అయినప్పటికీ బుద్ధుణ్ణి చూడగానే ఆ ఏనుగు శాంతించి అతనికి మోకరిల్లింది. ఒక చిత్రం కథనెలా చెప్పిందో చూశారా? ఈ కథ సందేశం ఏమై ఉంటుందో ఆలోచించండి.

చిత్రం 20.17: నాగార్జునకొండలో లభించిన ఈశిల్పంలో ఆరుగురు యువరాజులు, ఉపాలి అనే క్షురకుడు బౌద్ధ సంఘంలో ప్రవేశానికి అనుమతి పొందటం చూడవచ్చు. మానవత్వాన్ని బోధించేందుకుగాను, బుద్ధుడు ముందుగా సంఘంలోకి ఉపాలిని అనుమతించి తర్వాత మిగిలిన వాళ్ళని అనుమతించారు. బుద్ధునికి ఎడమవైపున చిన్న ఆసనంమీద కూర్చున్న ఉపాలిని చిత్రంలో చూడవచ్చు.

చిత్రం 20.18: సాంచీ నుంచి సేకరించిన ఈ శిల్పం గ్రామాలలోని దినచర్యను తెలుపుతుంది. ఈ అందమైన ఫలకం ఒక గ్రామంలో బుద్ధుని సందర్శనాన్ని తెలుపుతుంది. ఈ ఫలకంలో కనిపిస్తున్న ప్రజల దైనందిన కృత్యాలను పట్టికగా రాయండి. ప్రస్తుతం ఇలాంటి కృత్యాలను ఇప్పటి గ్రామాల్లో చూడగలమా? ఆలోచించండి.

"విహారాల"నేవి బౌద్ధభిక్షువులు నివసించిన సన్యాసుల పీఠాలు లేదా ఆవాసాలు. వీటిలో మతపరమైన విద్య నేర్పేవారు. సాధారణంగా విహారాల్లో బహిరంగ ఆవరణ ఉంటుంది. దాని చుట్టూ చిన్న గదులు ఉండేవి. మరొకవైపు ఒక చిన్న పూజా మందిరం లేదా ఒక స్థూపం లేదా బుద్ధుని ప్రతిమ ఉండేవి. ఈ పూజా మందిరాన్నే "చైత్యమ"ని, బౌద్ధ భిక్షువుల ప్రార్థనాస్థలమని అంటారు.

నాసిక్, కార్లేలలో గుహవిహారాలను కనుక్కొన్నారు. వీటిలోకూడా చెక్కిన కొన్ని అందమైన శిల్పాలు ఉన్నాయి.

SCERT TELANGANA

The other *viharas* were built with brick or stone blocks like in Takshashila, Nagarjunakonda and Nalanda, which became great places of learning. In Viharas, monks taught Buddhist scriptures to disciples. Along with imparting education in Viharas, monks also treated the physical ailments of people. We find many inscriptions from these viharas, which tell us that ordinary men and women – farmers, traders, soldiers, and artisans – made liberal donations for building and the other expenses of these viharas.

Buddhist holy places of learning also attracted the pilgrims from many other countries. Chinese pilgrims Fa-hi-an, Itsing and Hu- en-Tsang came to visit places associated with the life of the Buddha as well as famous monasteries.

Pilgrims are people who take up journeys to holy places of worship.

Hu-En-Tsang, and others spent time studying in Nalanda (Bihar), the most famous Buddhist monastery of the period. This is how he describes it:

"The teachers are men of the highest ability and talent. They follow the teachings of the Buddha in all sincerity. The rulers of the monastery are strict, and everyone has to follow them. Discussions are held throughout the day, and the old and the young mutually help one another. Learned men from different cities come here to clear their doubts. The gate keeper asks new entrants difficult questions. They are allowed to enter only after they have answered them. Seven or eight out of every ten are not able to answer."

20.2.2 Rock cut Chaityas and Early Temples

Traders, artisans and kings of the times of the Satavahanas donated generously to build unique kinds of chaityas and viharas in several places in Maharashtra like Karle, Bhaja, Kanheri and Nasik. These were built like caves on hill sides. Stone workers, carved rocks and reproduced the structures made by the carpenters with wood. They made large prayer halls, stupas and small rooms for monks – all made in rock. They also carved beautiful images of people and animals and some times of the Buddha. Look at these pictures of the Karle chaitya, which was built about 2100 years ago.

- Do you think the man and the woman shown in the sculpture had equal status? Give reasons.
- Which part of the chaitya do you think was carved out first and which part was carved the last?

Even then carpenters and masons made temples and chaityas with mud, wood and stones. Some of these temples were for gods like Krishna while others are for the Buddha.

SCERT, TELANGANA

తక్షశిల, నాగార్జునకొండ, నలంద వంటి మిగిలిన విహారాలను ఇటుకతో లేదా రాతితో నిర్మించారు. ఇవి గొప్ప విద్యా బోధన కేంద్రాలుగా రూపొందాయి. ఈ విహారాల్లో శిష్యులకు బౌద్ధ భిక్షువులు బౌద్ధగ్రంథాలను బోధించేవారు. కేవలం విద్యనే కాకుండా శారీరక రుగ్మతలకు కూడా భిక్షువులు ఈ విహారాల్లో చికిత్స చేసేవారు. ఈ విహారాల్లో చాలా శాసనాలు లభ్యమయ్యాయి. అనేకమంది స్త్రీలు, పురుషులు, రైతులు, వర్తకులు, సైనికులు, వృత్తిపనివారు ఈ విహారాల నిర్మాణానికి, వాటి నిర్వహణకు విరాళాలిచ్చేవారని ఈ శాసనాలు చెబుతున్నాయి.

బౌద్ధుల ఈ పవిత్ర విద్యాలయాలు ఇతర దేశాల నుండి అనేక మంది యాత్రికులను ఆకర్షించాయి. చైనా యాత్రికులు ఫాహియాన్, ఇత్సింగ్, హ్యూయన్ త్సాంగ్‌లు బుద్ధుని జీవితంతో సంబంధం కలిగిన ప్రాంతాలను, ప్రముఖ బౌద్ధసన్యాసుల విద్యాపీఠాలను సందర్శించేందుకు విచ్చేశారు.

పవిత్ర స్థలాలను పూజించేందుకు / దర్శించేందుకు వెళ్లే ప్రజలను **యాత్రికులు** అంటారు.

హ్యూయన్‌త్సాంగ్ తదితరులు ఆనాటి ప్రఖ్యాత బౌద్ధ సన్యాసుల విద్యాపీఠమైన నలందా (బీహార్)లో విద్యనభ్యసిస్తూ కాలం గడిపారు. దీన్ని గూర్చి అతను ఇలా వివరించాడు.

"ఇక్కడి ఉపాధ్యాయులందరూ అత్యంత సామర్థ్యం, నైపుణ్యం కలిగినవారు. వీరంతా బుద్ధుని బోధనలను చిత్తశుద్ధితో అనుసరించేవారు. ఈ విద్యా పీఠాల నియమాలు కఠినంగా ఉండేవి. వాటిని ప్రతి ఒక్కరూ విధిగా పాటించాలి. రోజంతా చర్చాగోష్టులు జరిగేవి. వృద్ధులు, యువకులు పరస్పరం సహకరించుకొనేవారు. తమ సందేహాలను నివృత్తిచేసుకొనేందుకు వివిధ నగరాలనుండి విద్యార్థులు ఇక్కడికి వచ్చేవారు. కొత్తగా వచ్చేవాళ్ళని కాపలాదారులు కఠినమైన ప్రశ్నలు వేసేవారు. వారు వాటికి సరైన సమాధానాలను ఇస్తేనే ప్రవేశానికి అనుమతించేవారు. పదిమందిలో ఏడు లేదా ఎనిమిది మంది ఆ ప్రశ్నలకు సమాధానాలు ఇవ్వలేకపోయేవారు".

20.2.2 రాతిని తొలచి నిర్మించిన చైత్యాలు - మొదటి దేవాలయాలు

శాతవాహనుల కాలంలో వర్తకులు, వృత్తి కళాకారులు, రాజులు ఒక ప్రత్యేక శైలిలో విహారాల నిర్మాణానికి విరాళాలిచ్చేవారు. ఇలాంటివి మహారాష్ట్రలో – ముఖ్యంగా కార్లే, భాజా, కన్హేరి, నాసిక్‌లలో చూడొచ్చు. పర్వత ప్రాంతాలలో వీటిని గుహలుగా నిర్మించేవారు. రాతిపనివారు ఉలి, సుత్తి ఉపయోగించి రాళ్ళను తొలిచి వడ్రంగులు తయారుచేసే నిర్మాణాలను పోలిన ఆకృతులను ఆవిష్కరించారు. వీళ్ళు పెద్ద ప్రార్థనా ప్రాంగణాలను, స్థూపాలను, బౌద్ధ భిక్షువుల కోసం చిన్నగదులను రాళ్ళలో నిర్మించేవారు. మనుషుల మరియు జంతువుల అందమైన ప్రతిమలను, కొన్ని సందర్భాలలో బుద్ధుని విగ్రహాలను కూడా వీళ్ళు చెక్కేవారు. 2100 సంవత్సరాలకు పూర్వం నిర్మించిన కార్లే చైత్యపు చిత్రాలను పక్క పేజీలో పరిశీలించండి.

- ఈ శిల్పాలలో స్త్రీ, పురుషులకు సమాన హోదా ఉందని మీరు భావిస్తున్నారా? కారణాలు చెప్పండి.
- ఈ చైత్యంలో మొదటగా ఏ భాగం చెక్కి ఉంటారు? చివరగా ఏ భాగం చెక్కి ఉండవచ్చని మీరు భావిస్తున్నారు?

ఈ కాలంలో కూడా వడ్రంగులు, తాపీపనివారు దేవాలయాల, చైత్యాల నిర్మాణంలో మట్టిని, చెక్కను, రాతిని ఉపయోగించేవారు. ఈ దేవాలయాల్లో కొన్ని కృష్ణునికి, మరికొన్ని బుద్ధునికి సంబంధించినవి ఉన్నాయి.

SCERT, TELANGANA

Fig. 20.19: Outside gate of Karle cave chaitya

Fig. 20.20: Inside a Chaitya



Fig. 20.21 & 20.22: Sculptures from Karle

Fig. 20.23: Early Buddhist temple from Sanchi

But they have not survived. At Sanchi in Madhya Pradesh, we get to see one of the earliest surviving stone temples. It is a very simple structure, with just a small room (called *garbhagriha*) in which the idol of the Buddha was kept, and a small open porch or *mandapa* with no walls but only pillars. The door and the pillars are beautifully carved. However, the temple has a flat roof without any tower or *shikhara* on it. It was built around 1600 years ago.

Keywords

Chaitya	Monks	Stupa
Relics	Vihara	Monastery

SCERT, TELANGANA

చిత్రం 20.19: కార్లే చైత్యపు వెలుపలి ద్వారం

చిత్రం 20.20: చైత్యపు లోపలి భాగం

చిత్రం 20.21, 20.22: కార్లే శిల్పాలు.

అయితే ఇవి ప్రస్తుతం పదిలంగా లేవు. మధ్యప్రదేశ్ లోని సాంచీవద్ద ప్రాచీన కాలపు రాతి ఆలయమొకటి పదిలంగా ఉంది. దీని నిర్మాణం సరళంగా ఉంది. గర్భ గృహ అని పిలిచే ఒక చిన్న గదిలో బుద్ధుని విగ్రహం ఉండేది. ఈ చిన్న తెరిచి ఉన్న వాకిలి లేదా మంటపం ఏవిధమైన గోడలు లేకుండా కేవలము స్తంభాలతో మాత్రమే ఉంది. ఈ స్తంభాలను అందంగా చెక్కారు. ఈ ఆలయ పైకప్పు సమతలంగా ఉంది. దీనికి ఏ విధమైన శిఖరమూ లేదు. దీన్ని 1600 సంవత్సరాలకు పూర్వం నిర్మించారు.



చిత్రం 20.23: సాంచీలోని ప్రాచీన బౌద్ధ ఆలయం

కీలకపదాలు

చైత్యం	బౌద్ధ సన్యాసులు	స్థూపం
అవశేషాలు	విహారం	ఆరామం

SCERT TELANGANA

IMPROVE YOUR LEARNING

1. Why do you think Ashoka chose lions and bulls for his pillars rather than cows or parrots? What animal would you have chosen if you were in his place? Give reasons for your choice.

X4G8V6

2. Many stupas of Andhra Pradesh are on the banks of rivers (like Salihundam, Nagarjunakonda, Amaravati etc). Why do you think the monks selected these places to build stupas?
3. Look at the sculpture showing the calming of the elephant. Who are the people watching the event from a height?
4. Why do you think only the rock cut viharas and chaityas have survived till today?
5. Compare the features of a Chaitya and a temple. Do you think the mode of worship in a Chaitya and a temple would be different?
6. Why are the Buddhist Stupas and Chaityas sacred?
7. How did the Buddhist monks probably use the Viharas and Chaityas?
8. Locate Buddhist and Jain sites on the outline map of Telangana.
9. Read the first para of page 170 (Vihara's were the ...... for the monks) and comment on it.

Project:

Visit a place of worship in your village or town and draw a sketch of the structure. Try to get the name of each part, its meaning and use. Prepare a report about this place of worship and conduct an exhibition in your class.

SCERT, TELANGANA

మీ అభ్యసనాన్ని మెరుగుపరచుకోండి

Z1G9Y7

1. అశోక చక్రవర్తి తన స్తంభాలపై గోవుల, లేదా రామచిలుకల శిల్పాలకు బదులుగా సింహాలనో లేదా ఎద్దులనో ఎందుకు ఎంపిక చేశాడు? అతని స్థానంలో మీరు ఉంటే ఏ జంతువును ఎంపిక చేస్తారు? మీ ఎంపికకు గల కారణాలు ఇవ్వండి.
2. ఆంధ్రప్రదేశ్‌లోని అనేక స్థూపాలు నదీ తీరాలలోనే ఉన్నాయి. (ఉదా: సాలిహుండం, నాగార్జునకొండ, అమరావతి మొదలైనవి) స్థూపాల నిర్మాణానికి భిక్షువులు/ సన్యాసులు, ఈ ప్రాంతాలనే ఎందుకు ఎంపిక చేశారు?
3. ఏనుగును శాంతపరిచే శిల్పంలో కొంతమంది కొంత ఎత్తులో ఉండి ఆ సంఘటనను గమనించడాన్ని చూడండి. ఆ ప్రజలు ఎవరని మీరు భావిస్తున్నారు?
4. రాతిని తొలచిన విహారాలు, చైత్యాలు ఈ నాటికీ పదిలంగా ఉండడానికి కారణం ఏమిటి?
5. చైత్యపు లక్షణాలను, దేవాలయాల లక్షణాలతో పోల్చండి. చైత్యంలో పూజావిధానానికీ, దేవాలయంలో పూజావిధానానికి తేడాలు ఉన్నాయా? ఏమిటి?
6. స్థూపాలను, చైత్యాలను బౌద్ధులు ఎందువల్ల పవిత్రమైనవిగా చూస్తారు?
7. విహారాలు, చైత్యాలు బౌద్ధ భిక్షువులకు ఎలా ఉపయోగపడ్డాయి?
8. తెలంగాణ పటంలో బౌద్ధ, జైన క్షేత్రాలను గుర్తించండి.
9. పేజి నెం.171 లోని 'విహారాలనేవి బౌద్ధ భిక్షువులు ...... ప్రార్థనా స్థలమని అంటారు' పేరాను చదివి, వ్యాఖ్యానించండి.

ప్రాజెక్టు

మీ గ్రామంలో గాని, పట్టణంలో గాని ఒక దేవాలయాన్ని సందర్శించి దాని నిర్మాణపు రేఖా చిత్రాన్ని గీయండి. ఆ నిర్మాణంలోని ప్రతి భాగం పేరూ, దాని ఉపయోగాన్ని, అర్థాన్ని రాసేందుకు ప్రయత్నించండి. ఆ దేవాలయం గురించి ఒక నివేదికను తయారు చేసి, మీ తరగతిలో ప్రదర్శించండి.

SCERT, TELANGANA